Plan local d'urbanisme

COMMUNE DE LE PALAIS

DÉPARTEMENT DU MORBIHAN

ORIENTATIONS D'AMÉNAGEMENT ET DE PROGRAMMATION

REVISION GÉNÉRALE APPROUVÉE LE 5 MARS

MODIFICATION SIMPLIFIÉE N°2 APPROUVÉE LE 24 SEPTEMBRE 2024



PIÈCE DU PLU

3

Cittânova

SOMMAIRE

I. PRÉAMBULE

Le contexte législatif et réglementaire.....5

II. OAP DES ZONES À URBANISER DU BOURG ET DU VILLAGE DE KERSABLEN

Principes d'aménagement communs.....8

Localisation des secteurs d'OAP.....12

Présentation des OAP.....13

III. OAP À VOCATION D'ACTIVITÉS ET D'ÉQUIPEMENTS

Présentation des OAP.....31

I - PRÉAMBULE

LE CONTEXTE LÉGISLATIF ET RÉGLEMENTAIRE DES ORIENTATIONS D'AMÉNAGEMENT ET DE PROGRAMMATION (OAP)

QU'EST-CE QU'UNE OAP ?

Les Orientations d'Aménagement et de Programmation sont un outil d'urbanisme du PLU qui permet de décliner plus précisément les objectifs du PADD sur des secteurs stratégiques du territoire. Elles permettent en particulier d'encadrer les futurs projets en définissant les grandes composantes des aménagements et les éléments à préserver ou à mettre en valeur à travers le projet.

Le contenu des OAP est principalement défini par les articles L.151-6 et L.151-7 du Code de l'Urbanisme qui précisent le champ d'application et le contenu que peuvent prendre les OAP.

L'article **L151-6 du code de l'urbanisme** indique que «les orientations d'aménagement et de programmation comprennent, en cohérence avec le projet d'aménagement et de développement durables, des dispositions portant sur l'aménagement, l'habitat, les transports et les déplacements.».

L'article **L.151-7 du code de l'urbanisme** précise que «les orientations d'aménagement et de programmation peuvent notamment :

1° Définir les actions et opérations nécessaires pour mettre en valeur l'environnement, notamment les continuités écologiques, les paysages, les entrées de ville et le patrimoine, lutter contre l'insalubrité, permettre le renouvellement urbain et assurer le développement de la commune;

2° Favoriser la mixité fonctionnelle en prévoyant qu'en cas de réalisation d'opérations d'aménagement, de construction ou de réhabilitation un pourcentage de ces opérations est destiné à la réalisation des commerces;

3° Comporter un échéancier prévisionnel de l'ouverture à l'urbanisation des zones à urbaniser et de la réalisation des équipements correspondants;

4° Porter sur des quartiers ou des secteurs à mettre en valeur, réhabiliter, restructurer ou aménager;

5° Prendre la forme des schémas d'aménagement et préciser les principales caractéristiques des voies et espaces publics

6° Adapter la délimitation des périmètres, en fonction de la qualité de la desserte, où s'applique le plafonnement à proximité des transports prévu aux articles L.151-35 et L.151-36.»

II - ORIENTATIONS D'AMÉNAGEMENT ET DE PROGRAMMATION DES ZONES À URBANISER DU BOURG ET DU VILLAGE DE KERSABLEN

① Orientation précisée dans le corps du texte de l'OAP secteur

VOCATION DOMINANTE DES ESPACES

- Espace destiné à la création de logements sous la forme d'une opération d'ensemble
- Espace destiné à la création de logements majoritairement sous des formes denses
- Espace naturel ou jardiné à préserver (jardins, espace vert, transition végétale, etc.)
- Espace destiné à un usage public ou mutualisé à l'échelle de l'opération (équipement, placette, terrain de jeux, etc.)
- Espace destiné à un usage public gérant les flux et les stationnements
- Espace destiné à la création de bâtiments d'activités
- Parcelles déjà construites
- Terrains destinés à des activités particulières

ORIENTATIONS LIEES A L'IMPLANTATION ET A LA FORME URBAINE

- Traiter les abords du site en contact avec la voie et cette dernière de manière à qualifier et marquer l'entrée dans le centre-bourg
- Assurer une transition harmonieuse avec les parcelles riveraines, en :
  - limitant les vis-à-vis et les ombres portées les plus gênantes
  - préservant voir en favorisant leur potentiel d'évolution (accès, position des constructions, etc.)
- Bâtiment destiné à être réhabilité, rénové ou détruit
- Positionnement préférentiel pour un espace public ou collectif (placette, cour commune, etc.)
- Positionnement préférentiel pour un espace public ou collectif à dominante jardiné (square, mail, etc.) autour duquel le bâti s'organise
- Exemple d'implantation des constructions à privilégier

ORIENTATIONS PAYSAGERES ET ENVIRONNEMENTALES

- Maintenir les haies ou arbres remarquables
- Assurer une transition en maintenant des ouvertures
- Assurer une transition végétale entre l'espace urbanisé et les espaces agricoles et naturels
- Créer un alignement d'arbres
- Arborer l'espace
- Positionnement préférentiel pour un point de collecte sélective
- Cône de vue à préserver
- Traitement qualitatif de la limite avec la rue

ORIENTATIONS LIEES AUX ACCES, A LA DESSERTE ET AU STATIONNEMENT

- Voie structurante à créer (position indicative)
- Voie de desserte à créer (position indicative)
- Possibilité de desserte complémentaire (position indicative)
- Liaison douce à créer (position indicative)
- Possibilité de liaison douce complémentaire (position indicative)
- P Positionnement préférentiel d'un espace de stationnement mutualisé
- Accès aux constructions mutualisé ou individuel (position indicative)
- Exemple d'emplacement préférentiel

PRINCIPES D'AMÉNAGEMENT COMMUNS À TOUTES LES ORIENTATIONS D'AMÉNAGEMENT ET DE PROGRAMMATION

1 - COMPOSITION URBAINE PRÉFÉRENTIELLE

Les secteurs de projet doivent être urbanisés sous la forme d'une opération d'ensemble, et doivent comprendre une programmation diversifiée, permettant l'accueil de tout type de population, notamment :

- Une offre de terrains à bâtir de tailles variées, permettant l'accueil de familles, en respectant une superficie moyenne compatible avec les objectifs de modération de la consommation d'espace.
- Garantir des logements adaptés aux jeunes ménages, aux foyers monoparentaux, aux séniors et/ou aux ménages aux faibles ressources.
- Un espace ouvert public ou commun à l'opération,
- Un réseau viaire interne traversant et un réseau de cheminements doux (piétons, vélos, etc.) connectés aux quartiers environnant.

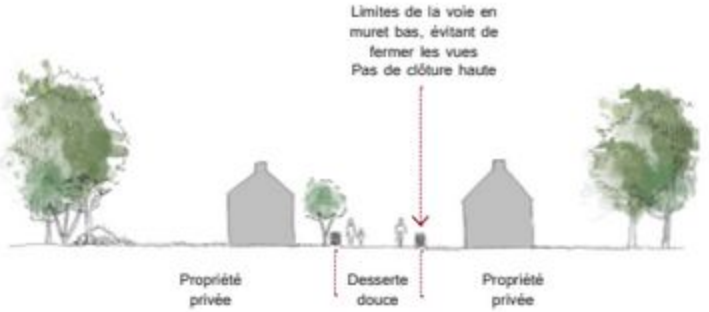

- L'intégration et la prise en compte du contexte notamment en terme de volumétrie et d'orientation des bâtiments environnants.

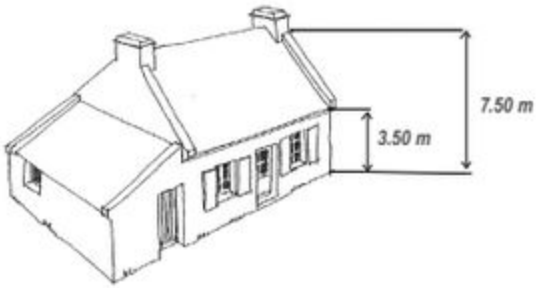

- L'implantation des nouvelles constructions devra prendre en compte les contraintes climatiques inhérentes à Belle-île, notamment les nuisances liées aux vents importants et l'optimisation de l'ensoleillement.

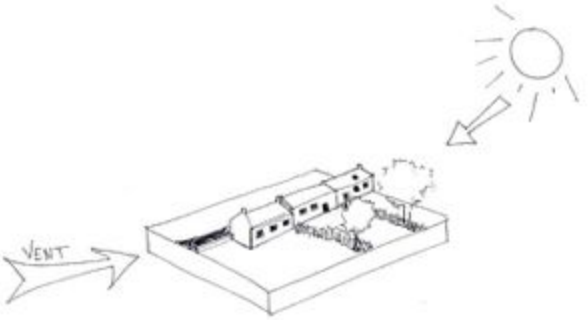

- L'implantation en milieu de parcelle est à proscrire puisqu'elle génère des formes urbaines pauvres. Le découpage classique d'un lotissement est à éviter.
  Les nouvelles constructions devront créer des alignements avec le tissu urbain existant par les bâtiments et les garages, abris ...
  L'implantation en limite de parcelle est conseillée, lorsqu'elle concorde avec le critère précédent, car elle protège les jardins et délimite l'espace privé de l'espace public.

Découpage en lot systématique à éviter

Ne prend pas en compte le contexte

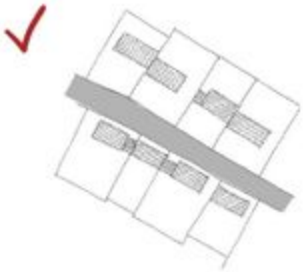

Respect de l'alignement

Surface de jardin importante

L'aménagement de la zone sera conditionné à une opération d'ensemble.

2 - DENSITÉ MINIMALE DES CONSTRUCTIONS

En cohérence avec les orientations générales du PADD et les objectifs du SCOT, une densité minimale doit être respectée :

	COMMUNE DE LE PALAIS
Objectifs de densité	**20** logements / hectare

3 - ÉQUILIBRE SOCIAL DE L'HABITAT

Les zones À Urbaniser à vocation d'habitat devront comprendre 100% de logements principaux en y intégrant des logements aidés ou sociaux, a minima 25%.

4 - PRINCIPES DE VOIRIE

La desserte interne automobile et piétonne, le découpage parcellaire et l'implantation des futures constructions seront envisagés de manière à prolonger les séquences existantes des rues de bourgs et à marquer leur caractère bâti et aggloméré.

A travers leurs tracés, leurs profils, leur aménagement, et leurs matériaux et son accompagnement végétal, les voies principales reçoivent un traitement adapté à leur fonction de transit au sein des espaces urbanisés du bourg, tandis que les dessertes secondaires constituent des espaces ouverts de qualité, à l'usage partagé, où la circulation se fait à faible vitesse.

Ces voies doivent également s'articuler avec les nouvelles constructions de manière à créer un tissu bâti de qualité, prolongeant celui du bourg existant et marquant le statut des différentes voies.

Exemples de liaisons douces recherchées

5 - PRINCIPES RELATIF A L'ESPACE PUBLIC

Les espaces publics et communs de l'opération chercheront à s'articuler de manière qualitative avec le tissu alentour et à contribuer à sa qualité, d'un point de vue fonctionnel, social et esthétique.

Autant que possible, les espaces publics et les cheminements seront conçus pour créer de grandes continuités douces à l'échelle du bourg.

6 - TRAITEMENT QUALITATIF DES LISIÈRES URBAINES

Les limites du secteur de projet en contact avec les parcelles déjà bâties seront étudiées pour limiter l'impact du projet pour les riverains, par exemple en privilégiant de répondre au bâti mitoyen par du bâti, aux jardins par des jardins, aux dégagements visuels par des espaces non bâtis, etc.

Lorsque le secteur de projet est en contact avec les espaces agricoles et naturels, une attention particulière sera portée au traitement de la lisière entre ces espaces et le site nouvellement urbanisé.

✗ Haie monospécifique taillée créant un rupture nette



✓ Haie vive composée de différentes strates de végétation et en continuité avec la végétation du jardin

7 - ACCÈS ET STATIONNEMENT

L'accès au site s'effectuera principalement par le réseau de desserte interne, tout en profitant des accès possibles par les voies existantes lorsque ceux-ci ne posent pas de problèmes de sécurité.

Les intersections avec les voies existantes seront traitées pour identifier les voies créées comme de véritables rues participant au réseau viaire du bourg.

L'offre de stationnement sur les parcelles privées et au sein de l'espace public / commun sera dimensionnée pour répondre aux besoins de l'opération. Elle intégrera des places destinées aux visiteurs.

Pour toute opération de deux logements, les stationnements et les dessertes devront être mutualisées pour limiter l'impact des véhicules en coeur d'opération et sur les parcelles privées (de manière à favoriser les espaces jardinés).

Exemple d'opération à Belle-Ile-en-Mer où le stationnement a été concentré à l'entrée de l'opération afin d'optimiser l'espace public sous forme d'une place au centre de l'opération.

Les circulations sont essentiellement piétonnes ou cyclistes, la voiture est rarement utilisée jusqu'au logement.

8 - GESTION DES EAUX PLUVIALES

Les zones imperméabilisées doivent être limitées au strict minimum pour favoriser l'infiltration naturelle des eaux pluviales sur les parcelles privées.

Il est conseillé une gestion des eaux pluviales à l'échelle du site par l'aménagement de noues, fossés, de bassins de rétention paysagers et de puits d'infiltration.

Les surfaces des espaces des cheminements, des trottoirs, des stationnements ainsi que des voies secondaires seront revêtues de matériaux drainants.

Tout projet doit répondre à un débit de fuite de rejet à l'échelle de la zone à urbaniser maximum de 3 l/s/ha intercepté, bassin versant amont compris. Le schéma des eaux pluviales annexé au PLU doit être respecté au sein de chaque OAP.

9 - PERFORMANCES ÉNERGÉTIQUES

Les opérations devront favoriser des orientations de bâtiments permettant une exploitation optimum des énergies naturelles, en favorisant notamment les ouvertures sur les façades au sud.

Il est également conseillé de favoriser le regroupement des bâtiments (mur mitoyen) pour limiter la perte énergétique et favoriser l'isolation du froid.

Les matériaux devront favoriser les économies d'énergie et respecter les normes thermiques en vigueur.

LOCALISATION DES SECTEURS D'OAP

ZOOM
8
3
4
7
1
12
2
9
5
10
6
11
0
200
400 m

1/ LE PALAIS - Avenue Jules Ferry

CARACTÉRISTIQUE ET VOCATION DU SITE

> Le secteur de projet est situé à proximité directe du coeur de bourg. La parcelle est localisée sur un point haut et domine le coeur de ville et le port.

> Le secteur de projet est en partie encadré par un espace boisé classé et par les remparts. Il s'aligne également sur l'Avenue Jules Ferry, et donne sur des espaces de stationnements de part et d'autre de celle-ci.

Superficie du site : 8509 m²

Densité à atteindre : 20 logements/ha

- Avenue Jules Ferry -

- Avenue Jules Ferry -

ORIENTATION D'AMÉNAGEMENT ET DE PROGRAMMATION

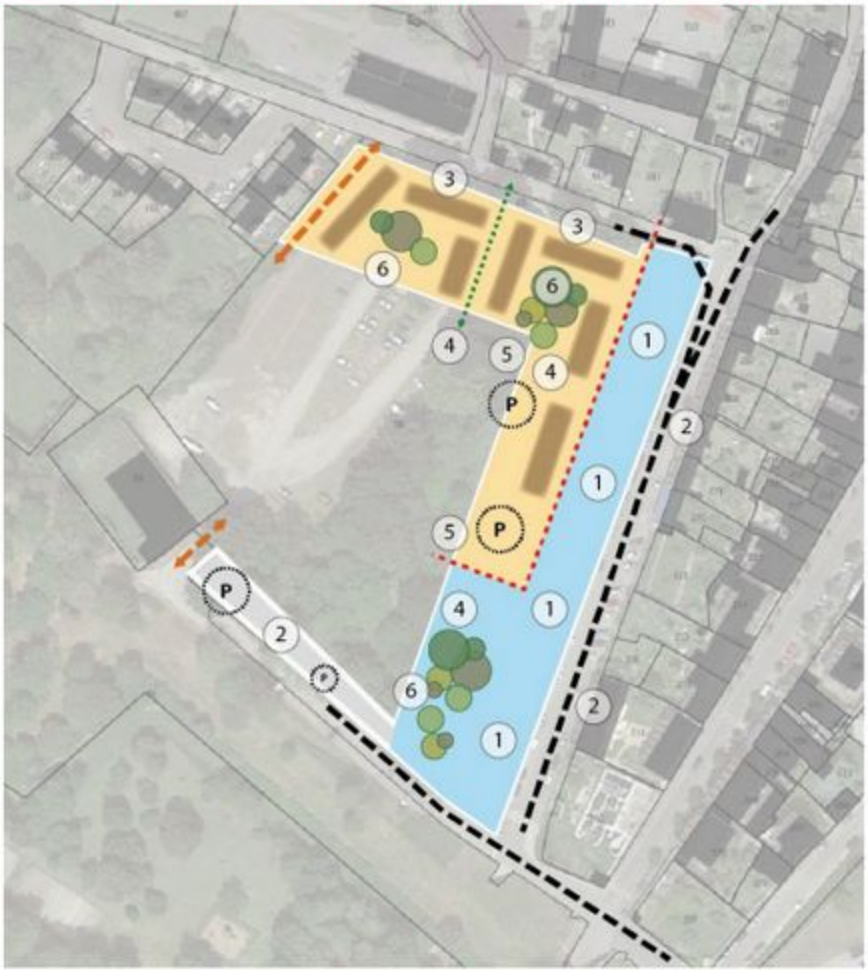

(1) Orientation précisée dans le corps du texte de l'OAP secteur

VOCATION DOMINANTE DES ESPACES

- Limite à titre indicatif entre deux opérations
- Espace destiné à la création de logements sous la forme d'une opération d'ensemble.
- Espace destiné à la création d'un pôle administratif et/ou d'équipements collectifs. Les logements de fonction y sont autorisés.
- (P) Positionnement préférentiel d'un espace de stationnement mutualisé
- Voie de desserte de l'aire de stationnement centrale (emplacement réservé n°9)

ORIENTATIONS PAYSAGERES ET ENVIRONNEMENTALES

- Espace naturel ou jardiné à préserver/créer (jardins, espace vert, transition végétale, etc.). Maintenir les haies ou arbres remarquables
- Exemple d'emplacement préférentiel du bâti
- Exemple de percées piétonnes

Cette OAP compte deux secteurs distincts :

Le **secteur ouest** aura une vocation d'habitat. Il sera aménagé sous la forme d'une opération d'ensemble pouvant être décomposée en plusieurs tranches. Ce secteur devra prévoir 20% de logements sociaux, soit 1 par tranche commencée de 5 logements.

Le **secteur est** sera destiné à la création d'un pôle administratif et/ou d'équipements collectifs. Les logements de fonction y sont autorisés.

1/ Proposer des constructions qui respectent la morphologie urbaine de l'avenue Jules Ferry, soit des constructions pouvant atteindre le R+1+C.
Le bâti pourra s'aligner le long de la voie principale afin de renforcer la perspective de l'avenue vers le cœur de ville. Les constructions en retrait peuvent être autorisées, sous réserve que la continuité en limite de voie soit assurée par la mise en place d'élément de type mur de clôture….
2/ Requalifier l'Avenue Jules Ferry afin de renforcer les usages piétons vers le cœur de ville et de canaliser l'emprise des flux de voitures. Des espaces de stationnements seront définis à l'extrémité sud de l'OAP ainsi que d'un côté de l'avenue afin d'y apporter une respiration.
3/ Sur la partie nord de l'OAP, l'habitat s'alignera sur la rue ou s'implantera en léger retrait. Il permettra de proposer un tissu plus résidentiel à proximité du centre-ville. Deux typologies de bâtis pourront être proposées au sein de ce secteur (R+1 et R+1+C).
4/ Aménager plusieurs percées piétonnes entre les bâtis afin de faciliter la traversée vers le cœur d'îlot. Cela permettra également de réduire l'impact visuel des nouveaux bâtis en créant des espaces de respiration. Des percées doivent également être réalisées entre les deux secteurs ouest et est.
5/ Stationner à proximité des nouveaux aménagements, créer des liens doux vers les constructions. Limiter l'impact visuel de la voiture au sein des nouvelles opérations bâties.
6/ Aménager le cœur d'îlot en espaces verts qualitatifs, ouverts, appropriables par tous. Ceux-ci seront traversés par des cheminements doux (reliés aux espaces de stationnements et aux rues principales bordant les opérations).
Des espaces verts privatifs pourront être destinés aux nouveaux logements.

CARACTÉRISTIQUE ET VOCATION DU SITE

> Le site de projet se situe sur la commune de Le Palais, dans le quartier de Bordilla. Le terrain est implanté en second par rapport à la Route Départementale de Bangor. La parcelle est marquée par un relief important.

> Des habitats se trouvent à proximité ainsi qu'une zone agricole, au sud de la parcelle.

Superficie du site : 5428 m²

Densité à atteindre : 20 logements/ha

- Route de Bangor -

- Route de Bangor -

ORIENTATION D'AMÉNAGEMENT ET DE PROGRAMMATION

> L'opération devra prévoir 20% de logements sociaux, soit 2 par tranche commencée de 10 logements.

1/ La desserte de l'opération s'organisera par le Sud. Il s'agira d'un accès mutualisé avec celui existant. 2/ En coeur d'opération, une place publique jouxte une zone de stationnements. Cela permet d'apporter des espaces de convivialité, des espaces ludiques et appropriables par tous en coeur d'opération.
3/ Un cheminement doux se raccroche également à cette placette et permet de traverser l'opération et d'accéder au jardin collectif créé à l'ouest du projet. Les liens doux sont donc sécurisés et qualitatifs. Le long de ce cheminement pourra être pris en charge la gestion des eaux pluviales.
4/ Un jardin partagé est positionné à l'ouest de la parcelle. Il sera planté et encadré par des haies, afin de limiter les vues vers les constructions existantes à proximité et de faciliter la biodiversité.
5/ Les nouvelles constructions seront implantées en alignement sur la voie (front bâti ou façade principale). Les maisons seront implantées de façon mitoyenne, voire jumelées. L'exposition des maisons individuelles devra être optimisée.
6/ Les terrains des nouvelles constructions seront encadrés par des haies, afin de permettre une meilleure insertion avec le tissu bâti existant qui se trouve à proximité.
7/ La haie existante sera conservée afin de limiter l'impact visuel de la nouvelle opération sur les bâtis existants en contrebas et d'assurer un corridor à la biodiversité
8/ Implanter une haie afin de délimiter la parcelle visuellement et physiquement.
9/ Structurer l'opération par une coulée verte qui garantira la gestion des eaux pluviales. Le cheminement doux vient s'appuyer sur cette coulée verte.
La gestion des eaux pluviales sera favorisée à l'échelle de l'opération.

Espace naturel ou jardiné à préserver (jardins, espace vert, transition végétale, etc.)

Espace destiné à un usage public ou mutualisé à l'échelle de l'opération (équipement, placette, terrain de jeux, etc.)

Espace destiné à un usage public gérant les flux et les stationnements

Assurer une transition végétale entre l'espace urbanisé et les espaces agricoles et naturels

Exemple d'emplacement préférentiel

CARACTÉRISTIQUE ET VOCATION DU SITE

Superficie du site : 12 509m²

Densité à atteindre : 20 logements/ha

> L'espace de projet est situé au nord du port de la commune de Le Palais. La parcelle est implantée sur un terrain marqué par le relief. A l'ouest, les terrains sont bâtis, au sud-est c'est une zone naturelle non bâtie. La nouvelle opération s'implante donc dans la continuité du tissu bâti. La parcelle est bordée par deux rues (au nord et au sud). Cette parcelle au Nord offre une vue directe sur le grand paysage.

- Haute Boulogne -

- Haute Boulogne -

ORIENTATION D'AMÉNAGEMENT ET DE PROGRAMMATION

1/ Une voirie traversante entre la Route de Roserières et de Haute Boulogne permet de desservir l'ensemble de la nouvelle opération et de centraliser les flux. Pour des raisons de sécurité, une entrée unique sera aménagée au Sud. La connection Nord pourra être aménagée à double sens.
2/ Un espace public central à l'opération est créé afin de proposer un espace de respiration en coeur d'îlot, qui se traduit comme un espace de stationnements et/ou un espace public.
Les nouvelles constructions s'implantent en alignement sur rue et en léger retrait. Elles devront s'intégrer à la pente. Les accès sont implantés de sorte à ce que les habitations bénéficient de la meilleure orientation pour les jardins : tournés vers le sud, voie d'accès au nord. Autour de la placette centrale, les constructions sont disposées autour d'une cour centrale.
Pour limiter les vis à vis et l'impact visuel de la nouvelle opération: une implantation de haies est prévue.
3/ Favoriser une bonne transition avec l'espace agricole situé au sud-est en implantant une haie.
4/ Dans un souci d'intégration, les limites extérieures de l'opération, sera plantée. Les habitations existantes sont principalement encadrées par des clôtures végétales et/ou murets.

① Orientation précisée dans le corps du texte de l'OAP secteur

VOCATION DOMINANTE DES ESPACES

- Espace destiné à la création de logements sous la forme d'une opération d'ensemble
- Espace naturel ou jardiné à préserver (jardins, espace vert, transition végétale, etc.)
- Espace destiné à un usage public ou mutualisé à l'échelle de l'opération (équipement, placette, terrain de jeux, etc.)
- Espace destiné à un usage public gérant les flux et les stationnements

ORIENTATIONS PAYSAGERES ET ENVIRONNEMENTALES

- Maintenir les haies ou arbres remarquables
- Assurer une transition végétale entre l'espace urbanisé et les espaces agricoles et naturels
- Exemple d'emplacement préférentiel

CARACTÉRISTIQUE ET VOCATION DU SITE

Superficie du site : 8840 m²

Densité à atteindre : 20 logements/ha

> Le site de projet est situé au nord ouest du port de la commune de Le Palais.

> Le site est marqué par le relief et offre donc une vue ouverte sur le grand paysage. Le site est encadré par de l'habitat existant type maisons pavillonnaires et une zone naturelle enclose par une végétation relativement dense.

- Route de Sauzon -

- Chêne vert-

ORIENTATION D'AMÉNAGEMENT ET DE PROGRAMMATION

1/ La desserte principale de l'opération se fera via la voie de Roz Cailloz. La haie existante sera préservée au maximum.

A l'entrée de l'opération, la zone est plantée, de sorte à conserver l'identité actuelle du quartier: une zone où les bâtis sont implantés en recul de la voie, annoncés par la présence de végétation en bord de voie. Cela permet également de qualifier l'entrée d'opération de manière qualitative.

Les nouvelles constructions s'implanteront en front bâti aligné sur la rue afin d'optimiser leur orientation. Le terrain étant contraint par une forme particulière, les parcelles individuelles seront traitées en lanières.

2/ Favoriser une bonne transition avec l'espace naturel situé à l'est de la zone de projet.

L'aménagement du secteur devra épouser au mieux la topographie afin de garantir une gestion des eaux pluviales optimisée.

3/ Préserver les arbres remarquables au sein de l'opération notamment le chêne vert.

① Orientation précisée dans le corps du texte de l'OAP secteur

VOCATION DOMINANTE DES ESPACES

- Espace destiné à la création de logements sous la forme d'une opération d'ensemble
- Espace naturel ou jardiné à préserver (jardins, espace vert, transition végétale, etc.)
- Espace destiné à un usage public ou mutualisé à l'échelle de l'opération (équipement, placette, terrain de jeux, etc.)
- Espace destiné à un usage public gérant les flux et les stationnements

ORIENTATIONS PAYSAGERES ET ENVIRONNEMENTALES

- Maintenir les haies ou arbres remarquables
- Assurer une transition végétale entre l'espace urbanisé et les espaces agricoles et naturels
- Exemple d'emplacement préférentiel

CARACTÉRISTIQUE ET VOCATION DU SITE

> La zone de projet est située au sud de la commune de Le Palais, au sud du quartier de Bordilla. Le terrain est encadré par un supermarché, des équipements scolaires et sportifs, ainsi que par des habitats de type pavillonnaires. Le lieu est donc stratégique pour le développement d'une zone d'habitats. Au sud du terrain, un bandeau étroit fait partie d'une zone naturelle. Le relief est peu marqué sur le terrain.

> Une grande partie de cette zone de projet a déjà été esquissée.

Superficie du site : 40561 m²

Densité à atteindre : 20 logements/ha

- Route de Borthelo -

- La Grande Prairie -

ORIENTATION D'AMÉNAGEMENT ET DE PROGRAMMATION

> L'opération devra prévoir 25% de logements sociaux, soit 1 par tranche commencée de 4 logements.

1/ La voirie principale est composée de deux accès situés Route de Borthelo.
2 / Des espaces publics sont implantés au sud, au nord ainsi qu'à l'est du site. Ils permettent d'offrir des espaces communs à la nouvelle opération. Ceux-ci se traduisent également comme des espaces de stationnements et/ou un espace public, aux usages variés.
3 / Des cheminements doux traversent l'ensemble de la nouvelle opération. Ils permettent de faciliter l'accès aux équipements ainsi qu'au centre-bourg.
4 / Les constructions incluent des logements collectifs en R+1, de l'habitat individuel ainsi que de l'habitat partagé. L'espace est arboré afin de créer des respirations au sein du tissu urbain.
Un espace dédié aux stationnements est implanté à l'entrée de l'opération,pour recevoir du stationnement.
5 / Un espace arboré est présent au nord est du site permettant de conserver une certaine intimité avec le commerce situé à proximité directe de l'opération.
6 / Implantation du bâti perpendiculairement à la voie en front bâti continu avec espace jardiné à l'avant exposé plein sud.

① Orientation précisée dans le corps du texte de l'OAP secteur

VOCATION DOMINANTE DES ESPACES

- Espace destiné à la création de logements sous la forme d'une opération d'ensemble
- Espace naturel ou jardiné à préserver (jardins, espace vert, transition végétale, etc.)
- Espace destiné à un usage public ou mutualisé à l'échelle de l'opération (équipement, placette, terrain de jeux, etc.)
- Espace destiné à un usage public gérant les flux et les stationnements

ORIENTATIONS PAYSAGÈRES ET ENVIRONNEMENTALES

- Maintenir les haies ou arbres remarquables
- Assurer une transition végétale entre l'espace urbanisé et les espaces agricoles et naturels
- Exemple d'emplacement préférentiel

CARACTÉRISTIQUE ET VOCATION DU SITE

> Le site de projet se situe au sud de la commune de Le Palais. Le terrain est encadré d'un secteur d'habitats au sud de la parcelle et est ouvert au nord sur une zone agricole. Des haies sont présentes sur le site et pourront en partie être conservées.

> Une esquisse a déjà été réalisée sur cette zone. Un projet neuf est en cours de réalisation sur le terrain voisin.

Superficie du site : 5474 m²

Densité à atteindre : 20 logements/ha

- Borthelo -

ORIENTATION D'AMÉNAGEMENT ET DE PROGRAMMATION

1/ La desserte de l'opération s'effectura à l'Ouest.

2/ Un espace public et paysager de type placette est créé à l'entrée ouest de l'opération. Il est encadré d'une zone engazonnée. Ces espaces permettent d'offrir une respiration en coeur d'opération ainsi qu'un espace sécurisé et appropriable par tous.

3/ Les nouvelles constructions seront implantées en respectant la topographie du site et selon une orientation optimale Est/Ouest.

4/ Au sud de l'opération, préserver les haies arbustives existantes pour limiter l'impact visuel des nouvelles constructions avec l'environnement immédiat.

5/ A l'est, implanter une haie arbustives entre cette zone de projet et le projet voisin. Cela permet d'implanter une limite visuelle et physique entre les deux opérations.

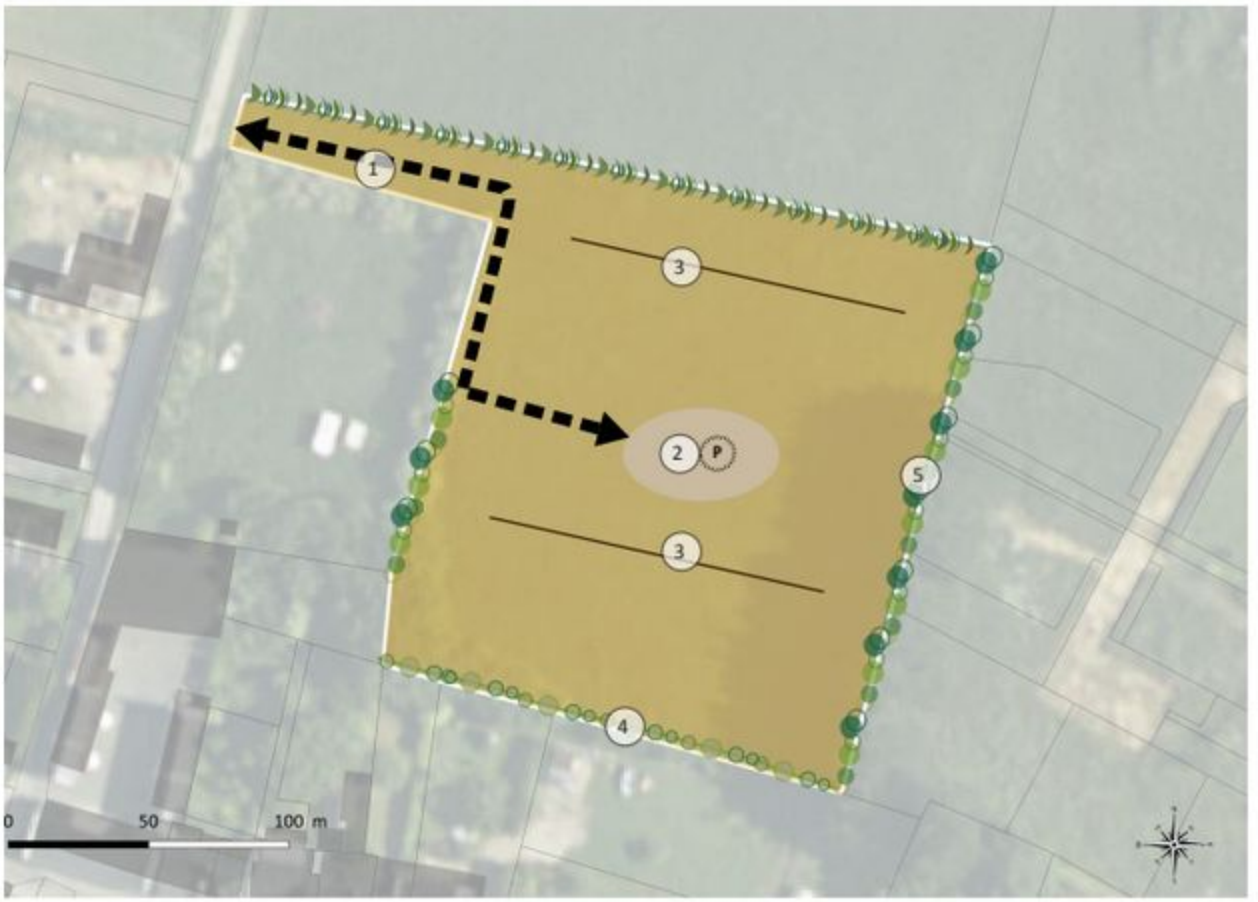

① Orientation précisée dans le corps du texte de l'OAP secteur

VOCATION DOMINANTE DES ESPACES

- Espace destiné à la création de logements sous la forme d'une opération d'ensemble
- Espace naturel ou jardiné à préserver (jardins, espace vert, transition végétale, etc.)
- Espace destiné à un usage public ou mutualisé à l'échelle de l'opération (équipement, placette, terrain de jeux, etc.)
- Espace destiné à un usage public gérant les flux et les stationnements

ORIENTATIONS PAYSAGERES ET ENVIRONNEMENTALES

- Maintenir les haies ou arbres remarquables
- Assurer une transition végétale entre l'espace urbanisé et les espaces agricoles et naturels
- Exemple d'emplacement préférentiel

CARACTÉRISTIQUE ET VOCATION DU SITE

> Le site de projet se situe au nord de la commune de Le Palais, dans un tissu où la densité est relativement élevée. Certains éléments comme les haies ou des murets pourront être conservés.

Ce projet vise à préserver le rythme des constructions établi sous la forme de longères ou de pavillons.

Superficie du site : 4575m²

Densité à atteindre : 20 logements/ha

- Vue satellite du site -

- Accès existant à l'ouest du site -

ORIENTATION D'AMÉNAGEMENT ET DE PROGRAMMATION

1/ L'opération sera accessible au nord par la rue du Mor Braz et à l'ouest par la route des Glacis.
2/ Une voie de desserte fera la connexion entre ces deux accès.
3/ Cette voie de desserte devra desservir les trois constructions existantes au sud du site (80 – 90 – 102 chemin des Douaniers).
4/ Une liaison douce transversale devra irriguer le secteur.
5/ Les nouvelles constructions seront implantées selon une orientation du faitage Est/ Ouest.

① Orientation précisée dans le corps du texte de l'OAP secteur

VOCATION DOMINANTE DES ESPACES

- Espace destiné à la création de logements sous la forme d'une opération d'ensemble
- Espace naturel ou jardiné à préserver (jardins, espace vert, transition végétale, etc.)
- Espace destiné à un usage public ou mutualisé à l'échelle de l'opération (équipement, placette, terrain de jeux, etc.)
- Espace destiné à un usage public gérant les flux et les stationnements

ORIENTATIONS PAYSAGERES ET ENVIRONNEMENTALES

- Maintenir les haies ou arbres remarquables
- Assurer une transition végétale entre l'espace urbanisé et les espaces agricoles et naturels
- Exemple d'emplacement préférentiel

CARACTÉRISTIQUE ET VOCATION DU SITE

> Le site de projet se situe au nord de la commune de Le Palais, route de Haute-Boulogne. Le terrain est encadré par un secteur d'habitat à l'ouest. Le site est bordé par le périmètre de protection de 60m du dépôt d'hydrocarbure. Le relief est assez marqué sur le terrain. Des haies sont présentes sur le site et pourront en partie être conservées.

Superficie du site : 4725m²

Densité à atteindre : entre 3 et 4 logements

- Site vu du sud -

- Vue satellite du site -

ORIENTATION D'AMÉNAGEMENT ET DE PROGRAMMATION

1/ Une voirie traversante desservira l'opération.

2/ La mare sera préservée et intégrée à l'aménagement d'ensemble.

3/ Un cheminement doux au sud permettra de connecter le site aux autres quartiers.

L'aménagement devra intégrer la gestion des eaux de ruissellement à l'échelle de l'opération. Cela peut prendre la forme d'aménagements spécifiques (noues...) et/ou de zones non imperméabilisées pour permettre l'infiltration des eaux pluviales et de ruissellement.

Les bâtiments seront implantés selon des orientations permettant à la fois de s'adapter au cadre de vie (points de vue, pente...) et d'optimiser les performances énergétiques (orientation...) et limiter l'exposition aux nuisances liées à la voie.

① Orientation précisée dans le corps du texte de l'OAP secteur

VOCATION DOMINANTE DES ESPACES

- Espace destiné à la création de logements sous la forme d'une opération d'ensemble
- Espace naturel ou jardiné à préserver (jardins, espace vert, transition végétale, etc.)
- Espace destiné à un usage public ou mutualisé à l'échelle de l'opération (équipement, placette, terrain de jeux, etc.)
- Espace destiné à un usage public gérant les flux et les stationnements

ORIENTATIONS PAYSAGERES ET ENVIRONNEMENTALES

- Maintenir les haies ou arbres remarquables
- Assurer une transition végétale entre l'espace urbanisé et les espaces agricoles et naturels
- Exemple d'emplacement préférentiel
- Cheminement doux à prévoir

CARACTÉRISTIQUE ET VOCATION DU SITE

> La zone de projet est située au sud de la commune de Le Palais, au sud de la Grande Prairie, au sein d'habitat de type pavillonnaire. Le lieu est donc stratégique pour le développement d'une zone d'habitats.

Superficie du site : 5527 m²

Densité à atteindre : 20 logements/ha

- Site vu du Nord -

ORIENTATION D'AMÉNAGEMENT ET DE PROGRAMMATION

1/ Une voirie traversante desservira l'opération de la route de Borthélo à la rue de la Grande Prairie.
2/ Les bâtiments seront implantés selon des orientations permettant à la fois de s'adapter au cadre de vie (orientation est/ouest, jardins au sud…) et d'optimiser les performances énergétiques (orientation…).
3/ L'aménagement proposera des aménagements paysagers supports d'usages (lieu de détente et/ou de loisirs partagé) et de qualité et permettra des lieux de rencontres au coeur de l'opération.
4/ Les éléments végétaux situés au Sud seront préservés afin de garantir une intégration paysagère maximale.

L'aménagement devra intégrer la gestion des eaux de ruissellement à l'échelle de l'opération. Cela peut prendre la forme d'aménagements spécifiques (noues…) et/ou de zones non imperméabilisées pour permettre l'infiltration des eaux pluviales et de ruissellement.

① Orientation précisée dans le corps du texte de l'OAP secteur

VOCATION DOMINANTE DES ESPACES

- Espace destiné à la création de logements sous la forme d'une opération d'ensemble
- Espace naturel ou jardiné à préserver (jardins, espace vert, transition végétale, etc.)
- Espace destiné à un usage public ou mutualisé à l'échelle de l'opération (équipement, placette, terrain de jeux, etc.)
- Espace destiné à un usage public gérant les flux et les stationnements

ORIENTATIONS PAYSAGERES ET ENVIRONNEMENTALES

- Maintenir les haies ou arbres remarquables
- Assurer une transition végétale entre l'espace urbanisé et les espaces agricoles et naturels
- Exemple d'emplacement préférentiel
- Cheminement doux à prévoir

III - ORIENTATIONS D'AMÉNAGEMENT ET DE PROGRAMMATION À VOCATION D'ACTIVITÉS ET D'ÉQUIPEMENTS

10/ LE PALAIS - Le Gouerch

CARACTÉRISTIQUE ET VOCATION DU SITE

Superficie du site : 2,32 ha

Le site de projet est situé au sud de la commune de Le Palais. Le terrain s'inscrit sur une parcelle étendue entre deux voies et en continuité directe du site d'équipements sportifs et de loisirs de la commune.

A noter, la présence d'une zone humide au Sud du site qui devra être prise en compte pour le projet.

- Vue depuis le nord-est du site -

- Vue depuis le sud du site -

1/ Liaison douce rejoignant les équipements existants.

2/ Accès nord et sud possibles. Mutualiser les accès avec la partie Ouest.

3/ Zone humide à protéger et à intégrer au projet.

Orientation précisée dans le corps du texte de l'OAP secteur

VOCATION DOMINANTE DES ESPACES

- Espace destiné à la création de bâtiments d'activités
- Espace naturel ou jardiné à préserver (jardins, espace vert, transition végétale, etc.)
- Espace destiné à un usage public ou mutualisé à l'échelle de l'opération (équipement, placette, terrain de jeux, etc.)
- Espace destiné à un usage public gérant les flux et les stationnements

ORIENTATIONS PAYSAGERES ET ENVIRONNEMENTALES

- Maintenir les haies ou arbres remarquables
- Assurer une transition végétale entre l'espace urbanisé et les espaces agricoles et naturels

11/ LE PALAIS - Mérézel

CARACTÉRISTIQUE ET VOCATION DU SITE

Le site de projet se situe au sud de la commune de Le Palais. Le terrain s'inscrit en continuité de la zone d'activité de Mérézel, zone artisanale inscrite au SCOT. La partie Sud-Est constitue le début du vallon et l'intégration du projet est primordiale afin de garantir une bonne insertion paysagère. La partie Nord, située le long de la route départementale, doit prévoir des aménagements paysagers afin de répondre à l'enjeu qualitatif de l'entrée de ville.

Superficie du site :33314 m²

- Merezel -

ORIENTATION D'AMÉNAGEMENT ET DE PROGRAMMATION

1/ Permettre une mutualisation des accès donnant sur les voies existantes.
2/ Assurer une transition paysagère qualitative avec le vallon situé en contre-bas afin de ne pas dénaturer le site.
3/ Développer un parking mutualisé permettant l'accueil de véhicules motorisés dans la mesure du possible.
4/ Aménager un écran végétalisé de 15 mètres et recul des constructions par rapport à la route départementale, celui-ci sera également support de biodiversité.
Les bâtiments seront implantés selon des orientations permettant à la fois de s'adapter au cadre de vie (points de vue, pente ...) et d'optimiser les performances énergétiques (orientation ...).
L'aménagement devra intégrer la gestion des eaux de ruissellement à l'échelle de la parcelle. Cela doit prendre la forme d'aménagements spécifiques (noues...) et/ou de zones non imperméabilisées pour permettre l'infiltration des eaux pluviales et de ruissellement.

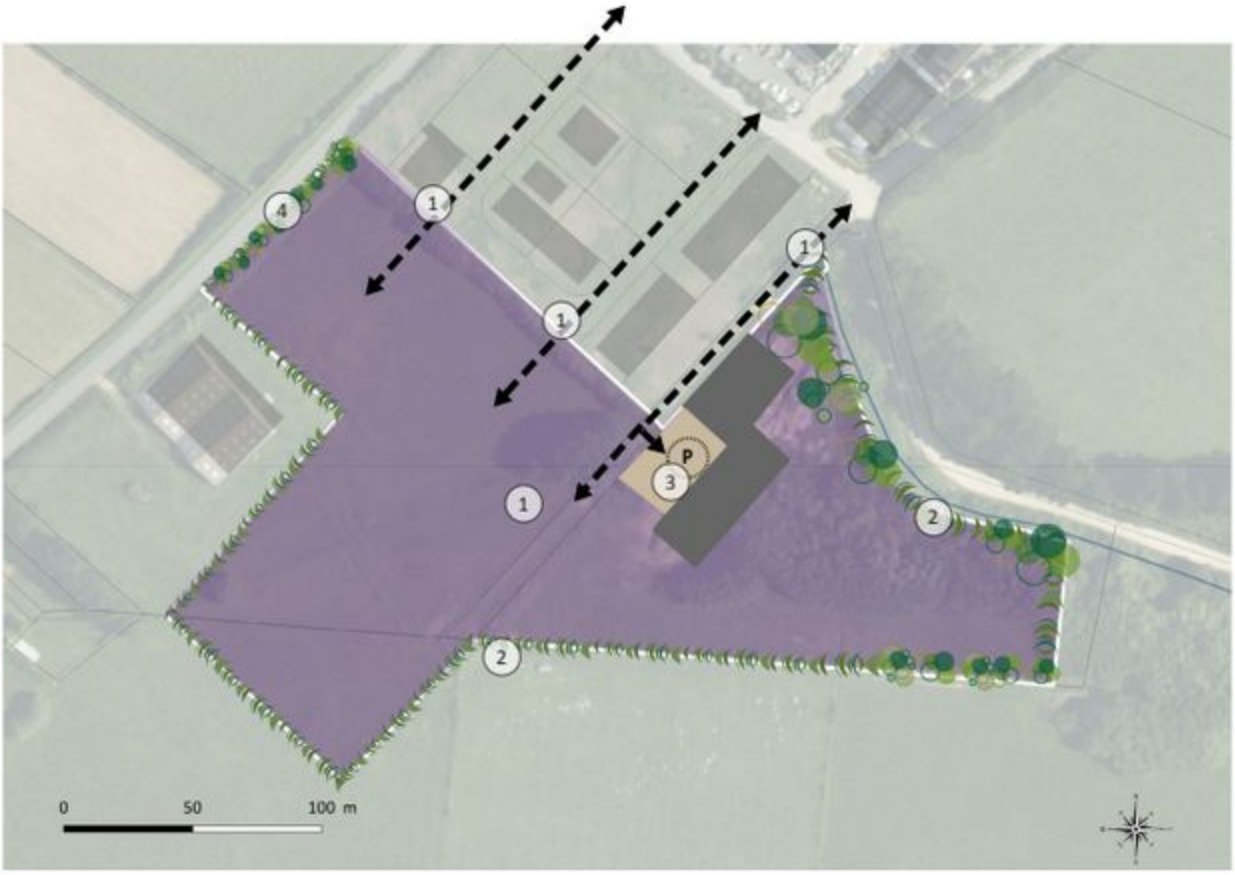

Orientation précisée dans le corps du texte de l'OAP secteur

VOCATION DOMINANTE DES ESPACES

- Espace destiné à la création de bâtiments d'activités
- Espace naturel ou jardiné à préserver (jardins, espace vert, transition végétale, etc.)
- Espace destiné à un usage public ou mutualisé à l'échelle de l'opération (équipement, placette, terrain de jeux, etc.)
- Espace destiné à un usage public gérant les flux et les stationnements

ORIENTATIONS PAYSAGERES ET ENVIRONNEMENTALES

- Maintenir les haies ou arbres remarquables
- Assurer une transition végétale entre l'espace urbanisé et les espaces agricoles et naturels

12/ LE PALAIS - Extension d'une zone d'activité

CARACTÉRISTIQUE ET VOCATION DU SITE

Superficie du site : 9 962 m²

Le site de projet se situe au nord-est du village de Kersablen sur la commune de Le Palais. Le terrain s'inscrit en continuité de la zone d'activité accueillant une grande surface commerciale.

L'intégration du projet est primordiale afin de garantir une bonne insertion paysagère, notamment par rapport au vallon situé à proximité.

- Kersablen-

ORIENTATION D'AMÉNAGEMENT ET DE PROGRAMMATION

1/ Permettre un accès au Nord du secteur.
2/ Assurer une transition paysagère qualitative avec le vallon situé en contre-bas afin de ne pas dénaturer le site.
Les bâtiments seront implantés selon des orientations permettant à la fois de s'adapter au cadre de vie (points de vue, pente ...) et d'optimiser les performances énergétiques (orientation ...).
L'aménagement devra intégrer la gestion des eaux de ruissellement à l'échelle de la parcelle. Cela doit prendre la forme d'aménagements spécifiques (noues...) et/ou de zones non imperméabilisées pour permettre l'infiltration des eaux pluviales et de ruissellement.

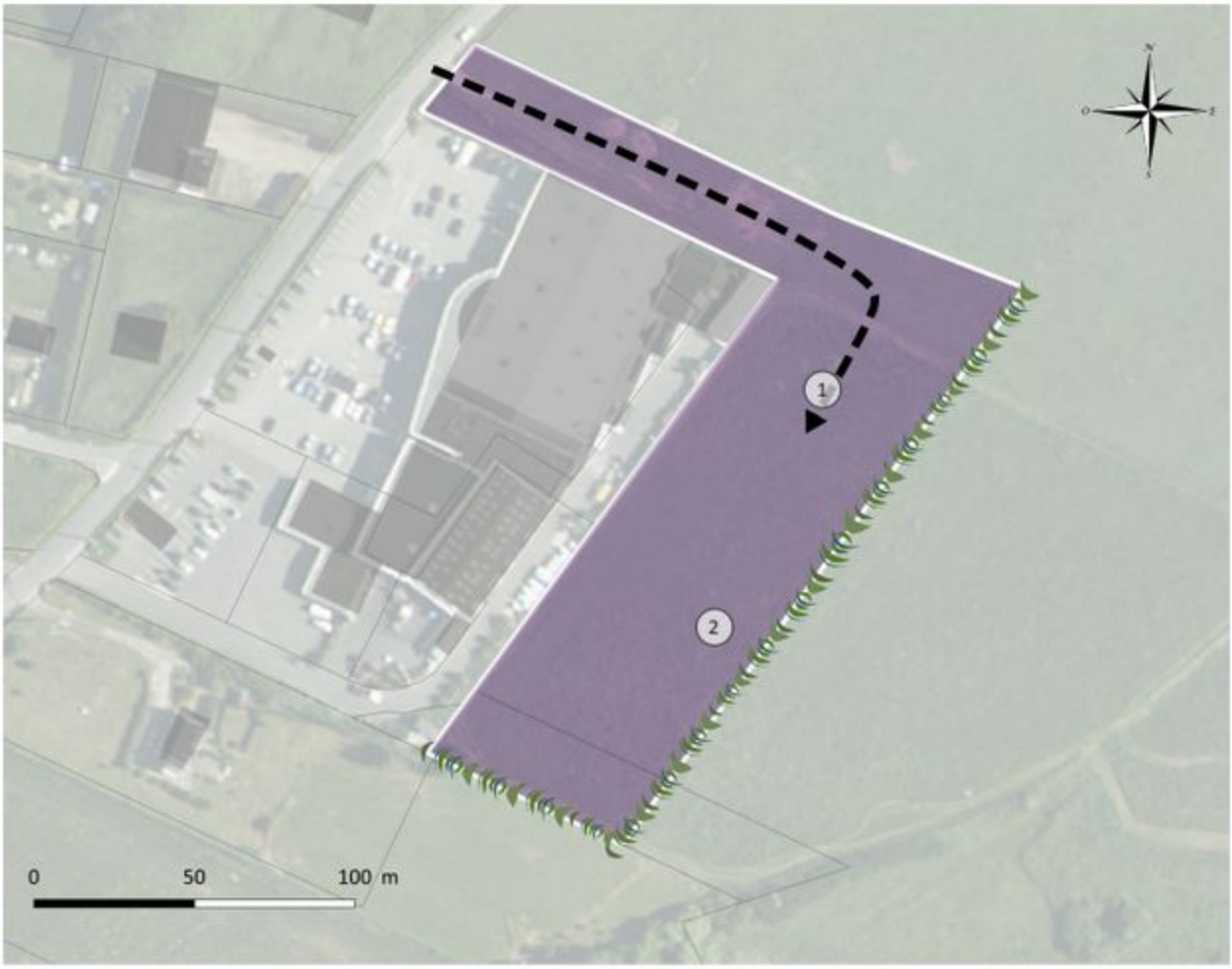

Orientation précisée dans le corps du texte de l'OAP secteur

VOCATION DOMINANTE DES ESPACES

- Espace destiné à la création de bâtiments d'activités
- Espace naturel ou jardiné à préserver (jardins, espace vert, transition végétale, etc.)
- Espace destiné à un usage public ou mutualisé à l'échelle de l'opération (équipement, placette, terrain de jeux, etc.)
- Espace destiné à un usage public gérant les flux et les stationnements

ORIENTATIONS PAYSAGERES ET ENVIRONNEMENTALES

- Maintenir les haies ou arbres remarquables
- Assurer une transition végétale entre l'espace urbanisé et les espaces agricoles et naturels