TITRE V - DISPOSITIONS PRECISANT DES ELEMENTS PARTICULIERS DU REGLEMENT DES DIFFERENTS ZONES

CHAPITRE 1 : DISPOSITIONS RELATIVES A LA TRAME VERTE ET BLEUE, AU PAYSAGE, AUX RISQUES ET A LA LOI LITTORAL

ESPACES BOISES CLASSES

Les terrains indiqués aux documents graphiques sont classés espaces boisés à conserver, à protéger ou à créer en application des dispositions de l'article L.113-3 du code de l'urbanisme.

Ce classement interdit tout changement d'affectation ou tout mode d'occupation du sol de nature à compromettre la conservation, la protection ou la création des boisements. Nonobstant toutes dispositions contraires, il entraîne le rejet de plein droit de la demande d'autorisation de défrichement prévue par l'article L.311-2 du code forestier.

Sauf application des dispositions de l'article L.113-3 du code de l'urbanisme, ces terrains sont inconstructibles à l'exception des bâtiments strictement nécessaires à l'exploitation des bois soumis au régime forestier.

HAIES AU TITRE DU L151-19 DU CODE DE L'URBANISME

Les haies protégées repérées sur le document graphique doivent être conservées. Tout aménagement, modification du sol ou construction à moins de 5 mètres de ces éléments doit faire l'objet d'une déclaration préalable. Ils pourront être refusés s'ils sont de nature à mettre en péril la pérennité de l'élément. Pour les haies, les coupes d'arbres de haut jet arrivé à maturité ou malades (sous réserve que chaque arbre abattu soit renouvelé avec des plants d'essences locales), l'ébranchage des arbres d'émonde et de têtards et les interventions sur les cépées d'arbres ou d'arbustes respectant l'essouchement et assurant le renouvellement de végétaux sont considérées comme des opérations courantes dispensées de formalité.

La réduction partielle d'une haie ou d'un alignement est autorisée si l'état phytosanitaire des sujets concernés représente un risque pour la sécurité des biens et des personnes, et à condition qu'il soit remplacé par un plant d'espèces autorisées.

L'implantation de certaines espèces invasives et potentiellement invasives sont à éviter pour les atteintes qu'elles occasionnent sur les habitats : le baccharis, la cinéraire maritime, l'herbe de la Pampa, la griffe de sorcière, l'éléagnus. Le cupressus est également à éviter.

ELEMENTS DE PAYSAGE AU TITRE DU L151-19 DU CODE DE L'URBANISME

Les terrains indiqués au document graphique sont classés en éléments de paysage au titre de l'article L151-19 du Code de l'Urbanisme. Le classement permet d'identifier et localiser les éléments paysager à protéger, à conserver, à mettre en valeur ou à requalifier. Ces espaces font l'objet d'un régime d'exception prévu à l'article L.421-4 du Code de l'Urbanisme pour les coupes et abattages d'arbres.

ESPACES ET SECTEURS CONTRIBUANT AUX CONTINUITES ECOLOGIQUES PROTEGES AU TITRE DU L151-23 DU CODE DE L'URBANISME

Etangs, plans d'eau et autres zones humides identifiées

Les zones humides sont repérées sur le document graphique.

Toutes les constructions y sont par défaut interdites, ainsi que les affouillements et les exhaussements du sol, lorsqu'ils sont de nature à altérer une zone humide avérée. Pour les projets qui s'implantent en limite d'une zone humide identifiée au document graphique, il sera demandé de délimiter précisément la zone humide dégradée et d'estimer la perte générée en termes de biodiversité.

La dégradation de zones humides, lorsqu'elle ne peut être évitée, fera l'objet de compensations compatibles avec les modalités définies par le SDAGE et en proportion de leurs intérêts écologique et hydraulique, afin de rechercher une équivalence patrimoniale et fonctionnelle.

Protection des abords de cours d'eau

Les constructions et aménagements conduisant à une artificialisation du sol devront observer un recul minimal de 35 mètres par rapport aux cours d'eau et espaces en eau identifiés sur le document graphique. Sauf en zone U où le recul sera de 5m.

Cette règle ne s'applique pas pour :

- Les quais et aux berges maçonnées, ainsi que pour les constructions nouvelles séparées du cours d'eau ou de l'espace en eau par une route ou un espace déjà imperméabilisé.

- Les constructions et aménagements nécessitant la proximité de l'eau

- Les équipements et aménagements publics ou d'intérêt collectif.

LES ZONES DE PRESOMPTION DE PRESCRIPTIONS ARCHEOLOGIQUES

Dans les secteurs identifiés sur le document graphique comme « *zones de présomption de prescriptions archéologiques* », les opérations d'aménagement affectant le sous-sol peuvent faire l'objet de prescriptions archéologiques préalables.

Pour rappel, les dispositions réglementaires et législatives ci-dessous doivent être considérées en matière de protection et de prise en compte du patrimoine archéologique :

- Code du Patrimoine et notamment les articles R.523-1, R.523-4, R.523-8, R.522-5, L.522-4, L.5231-14 ;
- Code de l'Urbanisme : R.111-4 ;
- Code de l'Environnement : L.122-1 ;
- Code Pénal : 322-3-1, 2°.

L'ensemble des zones de prescription archéologique sont identifiées et cartographiées en annexe du présent document.

LE RISQUE DE SUBMERSION MARINE

Dans les secteurs identifiés au plan de zonage concernés par le risque de submersion marine, la constructibilité est limitée. Sont seuls autorisés les travaux liés aux réseaux et voiries.

En zone de risque de submersion marine, les activités de campings ne sont autorisées qu'entre le 15 mai et le 15 octobre, pour des questions de sécurité.

Y est interdit l'installation de HLL ainsi que le gardiennage de résidence mobile de loisir ou de caravanes hors saison.

LES ESPECES VEGETALES DU TERRITOIRE

Il est recommandé d'utiliser des espèces non allergisantes ou réputées peu allergisantes pour réalisation des haies ou des massifs.

Les arrêtés préfectoraux suivants doivent être pris en considération :

- Arrêté préfectoral du 1er avril 2019 relatif à la lutte contre les ambroisies à feuilles d'armoise, à épis lisses et trifide, ainsi que contre la berce du Caucase.
- Arrêté préfectoral du 31 juillet 2020 relatif à la lutte contre les baccharis

CHAPITRE 2 : DISPOSITIONS RELATIVES AUX CENTRALITES COMMERCIALES

Les mesures édictées ci-après rentrent dans le champ d'application du SCoT du Pays d'Auray.

Le plan de zonage définit une centralité commerciale à l'extérieur de laquelle les activités entrant dans le champ d'application du volet commercial du SCoT sont interdites. A l'inverse, le plan de zonage définit une centralité commerciale à l'intérieur de laquelle les activités suivantes seront uniquement autorisées :

Préalable : les activités commerciales concernées par les dispositions commerciales du DOO et du DACOM :

Champ d'application du volet commerce du SCoT et du DAC	Activités exclues
Les activités de commerce de détail c'est-à-dire toute prestation avec un acte final d'achat d'un service ou d'un bien impliquant une transaction financière en direct ou dématérialisée (incluant les drives). Sans caractère d'exhaustivité, il est possible de distinguer les filières de commerces suivantes : **Alimentaire :** commerces d'alimentation générale, épicerie, fruits et légumes, vins et spiritueux, crémerie, fromagerie, cafés, bonbons, les poissonneries, les boucheries, charcuteries, traiteurs, les boulangeries. **Culture-loisirs :** fleurs, tabac, presse, librairie, photographe, jardinerie, informatique, sport. **Hygiène-santé-beauté :** coiffeur, institut de beauté, parfumerie, opticien, pharmacie et parapharmacie. **Equipement de la maison :** électroménager, tv-hifi, décoration, art de la table, linge de maison, bricolage, quincaillerie, meubles, brocantes. **Equipement de la personne :** vêtements, chaussures, bijouterie, maroquinerie, horlogerie, mercerie, dépôt vente. **Les services aux particuliers :** pompes funèbres, pressing, cordonnerie, toilettage pour chien, tatouage, agence immobilière, banque, assurance, auto-école, location et réparations diverses.	*Sont exclues du champ d'application des règles du volet commerce du SCoT et du DAC les activités suivantes :* • Les café-hôtel-restaurant y compris les campings • Le commerce de gros ayant principalement comme clientèle des professionnels • La vente directe de produits agricoles et maritimes domiciliée sur le lieu de production • Les stations de distribution de carburants • Les concessionnaires automobiles, camping-car, garages, nautisme, accastillage, motocycles et motoculture de plaisance • Les cinémas, bowling, parc de loisirs, salle de fitness • Les pépinières avec espace de production *L'exclusion de ces activités est justifiée dans la mesure où elles répondent à des logiques d'implantation différentes et considérées comme ayant moins d'impact en termes d'aménagement du territoire.*

CONDITIONS D'AGRANDISSEMENT DES ACTIVITES HORS LOCALISATIONS PREFERENTIELLES (PAGE 3 DOO)

L'évolution des activités commerciales existantes sont autorisées dans la limite de 20% de la surface de plancher à la date d'approbation du PLU. Les changements d'activités commerciales ne nécessitant pas de travaux sont admis dans la mesure où ils n'induisent pas de modification significative des flux routiers et de personnes.

Les restrictions d'implantation commerciale définies dans le SCoT ne s'appliquent pas aux situations spécifiques des show-room ou magasin d'usine qui s'appuient sur une activité artisanale ou industrielle et lorsque ce local représente moins de 15 % de la surface bâtie de l'unité de production et dans la limite de 100 m² de surface de vente. Les produits commercialisés au sein de cet espace de vente devront être issus de l'activité qui lui est rattachée.

Un showroom est un lieu d'exposition, et éventuellement de vente, des produits d'un fabricant.
Les magasins d'usine sont définis ici comme des points de vente de détail positionnés sur le lieu de production et commercialisant les produits issus de cette production.

La mutation d'activité commerciale en activité non commerciale est interdite pour les linéaires commerciaux identifiés au plan de zonage du PLU.

CHAPITRE 3 : DISPOSITIONS RELATIVES AUX VOIES ET INFRASTRUCTURES ROUTIÈRES

TRACE INDICATIF DE VOIRIE SIGNALE AU TITRE DU L 151-38 DU CODE DE L'URBANISME

Au titre de l'article L151-38 du Code de l'Urbanisme, certains chemins et sentiers présentant un intérêt à être conservé, modifié ou à créer, bénéficient d'une mesure de protection particulière. Les occupations et utilisations du sol portant atteinte à l'objectif de conservation, modification ou création des chemins et sentiers identifiées et de leurs abords (comprenant les éléments participant à leur intégration paysagère et environnementale tels que les haies et talus) pourront être interdites.

Lorsque le terrain concerné par le projet de construction et d'aménagement est traversé par un tracé indicatif de voirie identifié sur le document graphique au titre de l'article L.151-38, le projet ne doit pas remettre en cause l'objectif pour lequel le tracé a été repéré ou offrir une solution alternative équivalente.

CHAPITRE 4 : REGLES RELATIVES AU CALCUL DES PLACES DE STATIONNEMENT

(Article 2.4 des chapitres des zones)

Article 2.4 des différentes zones

	Nombre de places minimum à prévoir
HABITATION	
Logement	Dans l'ensemble de la zone UA : 1 place par logement Pour les autres zones : 2 places par logement
Logement locatif social	1 place par logement
Hébergement	Selon la fréquentation de l'établissement
COMMERCE ET ACTIVITÉ DE SERVICE	
Artisanat et commerce de détail	Selon la fréquentation de l'établissement
Restauration	1 / 10 m² de salle de restauration Jusqu'à 100 m² de surface de plancher, il n'est exigé aucune place de stationnement.
Commerce de gros	1 / 100m² de surface de plancher Jusqu'à 100 m² de surface de plancher, il n'est exigé aucune place de stationnement.
Activités de services où s'effectue l'accueil d'une clientèle	1 / 100m² de surface de plancher Jusqu'à 100 m² de surface de plancher, il n'est exigé aucune place de stationnement.
Hébergement hôtelier et touristique	1 / chambre
Cinéma	Selon les besoins de l'activité
ÉQUIPEMENTS D'INTÉRÊT COLLECTIF ET SERVICES PUBLICS	
Locaux et bureaux accueillant du public des administrations publiques et assimilés	1 / 50m² de surface de plancher
Locaux techniques et industriels des administrations publiques et assimilés	Selon les besoins de l'activité
Etablissements d'enseignement, de santé et d'action sociale	Selon la fréquentation de l'établissement

Salles d'art et de spectacles	Selon la fréquentation de l'établissement
Equipements sportifs	Selon la fréquentation de l'établissement
Autres équipements recevant du public	Selon la fréquentation de l'établissement
AUTRES ACTIVITÉS DES SECTEURS SECONDAIRE OU TERTIAIRE	
Bureau	1 / 100m² de surface de plancher
Centre de congrès et d'exposition	Selon les besoins de l'activité

Les places de stationnement des automobiles réservées aux personnes à mobilité réduite

Installations neuves ouvertes au public

Un emplacement de stationnement est réputé aménagé lorsqu'il comporte une bande d'accès latérale :

- D'une largeur de 0,80 mètre ;
- Libre de tout obstacle ;
- Protégée de la circulation ;
- Sans que la largeur totale de l'emplacement ne puisse être inférieure à 3,30 mètres.

Les emplacements réservés sont signalés.

Le nombre de places est de 1 par tranche de 50 places, ou fraction de 50 places.

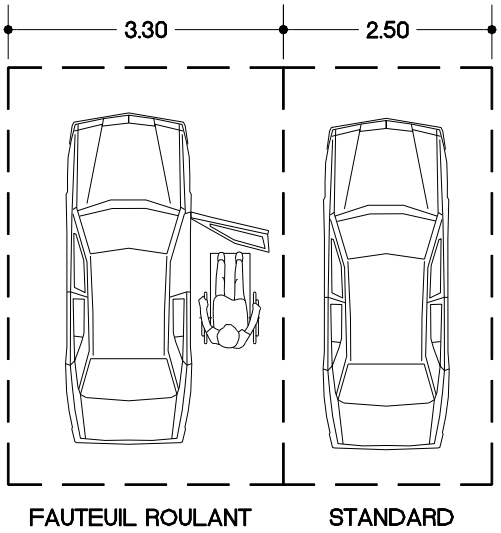

Installations neuves ouvertes au public

Le nombre de places à aménager sur le parc existant doit être déterminé en fonction de la ou des installations qu'il dessert, sans qu'un ratio fixe soit applicable.

Bâtiments d'habitation collectifs neufs

Le pourcentage minimum des places de stationnement d'automobiles destinées aux habitants et aux visiteurs, qui doivent être accessibles aux personnes handicapées, est fixé à 5%.

Ces places de stationnement à l'intérieur, sont dites adaptables, si après des travaux simples, elles peuvent satisfaire aux exigences suivantes :

La bande d'accès latérale prévue à côté des places de stationnement d'automobile aménagées, doit avoir une largeur d'au moins 0.80m sans que la largeur totale de l'emplacement ne puisse être inférieure à 3,30 m.

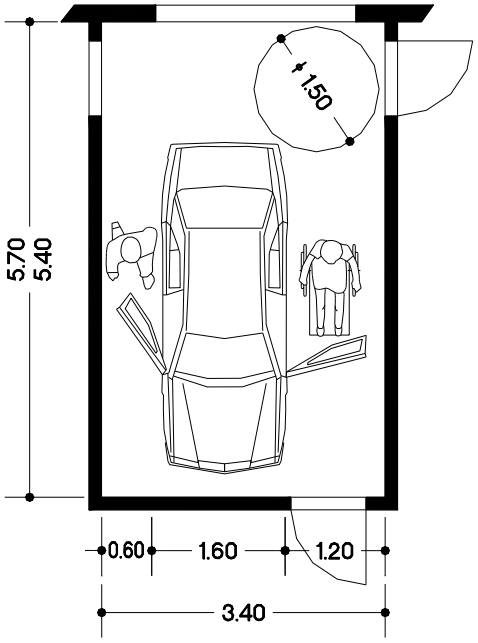

CHAPITRE 5 : REGLES RELATIVES AUX PRESCRIPTIONS ARCHITECTURALES DES BÂTIMENTS AUTRES QUE L'HABITATION

Les constructions devront s'intégrer à leur environnement. Les différents types d'occupation ou d'utilisation du sol visés aux articles 1.1 et 1.2 de la section 1 peuvent être refusés ou n'être accordés que sous réserve de l'observation de prescriptions spéciales, si les aménagements prévus, par leur situation, leur architecture, leurs dimensions ou leur aspect extérieur, sont de nature à porter atteinte au caractère ou à l'intérêt des lieux avoisinants, aux sites, aux paysages naturels ou urbains, ainsi que la conservation des perspectives monumentales.

Tous les bâtiments doivent s'intégrer parfaitement à leur environnement, notamment par :

- La grande simplicité de leur volume ;
- Des proportions correctes d'ensemble et de détail ;
- L'unité et la qualité des matériaux ;
- La couleur ;
- Une implantation soignée et étudiée en fonction de la topographie du terrain, de la végétation et des bâtiments voisins.

Dans ce but :

- Les bâtiments seront rectangulaires, la longueur avoisinant le double de la largeur ;
- Les toitures seront de préférence à deux rampants égaux, en longueur et en pente, cette dernière étant comprise entre 18° et 45° ;
- Le faîtage sera parallèle à la plus grande dimension de la construction ;
- Aucun fronton ou acrotère ne viendra masquer les rampants du toit ;
- Les matériaux de finition brillante ou réfléchissante sont interdits, tant en bardage vertical qu'en toiture,
- Les couleurs seront mates et choisies pour se fondre avec l'environnement. Les matériaux naturels (type bois, pierre, ardoise) ne seront pas altérés ;
- Les publicités, raisons sociales ou autres, seront disposées sur les parois verticales et devront rester discrètes.

CHAPITRE 6 : DISPOSITIONS RELATIVES À LA PRÉSERVATION DU PATRIMOINE BÂTI ET ARCHÉOLOGIQUE

Bâtiments repérés au titre du L 151-19 C.U.

Au titre de l'article L151-19 du Code de l'Urbanisme, certains bâtiments présentant un intérêt architectural et/ou patrimonial, bénéficient, par le biais du Plan Local d'Urbanisme intercommunal, d'une mesure de protection particulière.

Ainsi, les éléments bâtis à préserver, repérés sur les documents graphiques, sont soumis aux prescriptions suivantes :

- Tous travaux ayant pour effet de modifier ou de supprimer des constructions existantes repérées au titre de l'article L151-19 doivent être précédés d'une déclaration préalable de travaux ;
- Tous travaux effectués sur un bâtiment ou un ensemble de bâtiments repérés doivent contribuer à une sauvegarde de leurs caractéristiques culturelles, historiques et architecturales et à leur mise en valeur ;
- La démolition totale ou partielle est interdite. Une exception pourra néanmoins être autorisée pour les parties présentant un intérêt architectural et patrimonial moindre ;
- Les extensions ou constructions nouvelles sur l'unité foncière doivent être implantées de façon à mettre en valeur l'ordonnancement architectural du bâti existant. Elles pourront cependant être refusées si de par leur ampleur, leur nombre, ou leur différenciation avec le bâtiment repéré conduisent à une altération significative de ce dernier.

Le petit patrimoine a fait l'objet d'un inventaire complet et est annexé au présent règlement. Pour chacun des éléments listés, les règles précitées devront être respectées.

LES ZONES DE PRÉSOMPTION DE PRESCRIPTIONS ARCHÉOLOGIQUES

Dans les secteurs identifiés sur le document graphique comme « zones de présomption de prescriptions archéologiques », les opérations d'aménagement affectant le sous-sol peuvent faire l'objet de prescriptions archéologiques préalables.

ANNEXES

CHAPITRE N°1 : DEFINITIONS GENERALES

Accès : un accès est le point de passage aménagé en limite de terrain pour accéder à celui-ci depuis la voie ouverte à la circulation générale.

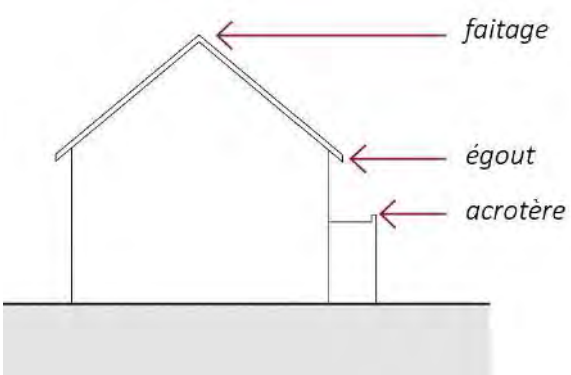

Acrotère : saillie verticale d'une façade, au-dessus du niveau d'une toiture-terrasse, ou d'une toiture à faible pente.
La cote de l'acrotère est une des cotes de référence qui a été choisie pour définir la hauteur maximale des constructions, particulièrement pour les constructions comportant des toitures terrasses**.**

Alignement : l'alignement est la détermination par l'autorité administrative de la limite entre le domaine public routier et les propriétés privées riveraines.

Annexe : tout édifice d'une emprise au sol maximale de 40 m2 détaché d'un bâtiment principal et non utilisé pour l'habitation (garage, atelier, abri à vélos, locaux techniques, dépendances diverses).

Clôture : ouvrage divisant ou délimitant un espace, servant le plus souvent à séparer deux propriétés : propriété privée et domaine public ou deux propriétés privées.

Comble : partie de l'espace intérieur, comprise sous les versants du toit et séparée des parties inférieures par un plancher.

Emplacement réservé : emplacement destiné à accueillir des équipements d'intérêt public (voirie, ouvrages publics d'infrastructure ou de superstructure, installations d'intérêt général, espaces verts, logement social). Toute construction ou occupation du sol non compatible avec leur destination future y est interdite.

Emprise au sol : rapport entre la surface obtenue par projection verticale sur un plan horizontal de toutes parties de la construction constitutives de surface de plancher et la surface de l'unité foncière (cf. art. R420-1 du Code de l'Urbanisme).

Extension : Agrandissement de la construction existante présentant des dimensions inférieures à celle-ci. L'extension peut être horizontale ou verticale (par surélévation, excavation ou agrandissement), et doit présenter un lien physique et fonctionnel avec la construction existante.

Façade : paroi extérieure d'une construction où se manifeste la présence de l'égout de toiture.

Faîtage : arête supérieure ou partie sommitale d'un toit, formée par la rencontre de deux versants.

Hauteur maximale : différence d'altitude maximale admise entre tout point de l'édifice et sa projection verticale sur le sol naturel avant travaux.

Limite séparative : limite entre propriétés privées d'une unité foncière, par opposition à la limite d'alignement.

Niveau le plus bas du niveau du terrain naturel : le niveau le plus bas du terrain naturel retenu dans le cadre d'un projet de construction sera en général celui existant à la date de dépôt de la demande, sauf si des exhaussements ou excavations ont été au préalable exécutés :

- en vue de la réalisation du projet, auquel cas le niveau antérieur du sol devra être retenu ;
- afin d'induire l'administration en erreur sur la conformité de la construction projetée à la réglementation d'urbanisme applicable, dans le cadre d'une intention frauduleuse.

Pignon : mur de construction dont la partie supérieure en forme de triangle supporte une toiture à deux versants.

Point médian : Point de référence de la face à partir duquel se calcule la hauteur. Il est utilisé dans le cas de terrain naturel en pente.

Reconstruction : construction d'un immeuble en remplacement d'un autre pour le même usage.

Restauration : ensemble de travaux, consolidations, reconstitutions ou réfections, tendant à conserver une construction.

En Retrait : se dit d'un élément de construction ou d'une construction placée en arrière de l'alignement.

Surface de plancher : surface de plancher close et couverte, sous une hauteur de plafond supérieure à 1,80 mètres. Cette surface est calculée à partir du nu intérieur pour ne pas pénaliser les efforts d'isolation par l'intérieur ou l'extérieur des bâtiments. Les aires de stationnement, les caves ou celliers, les combles et les locaux techniques sont, sous certaines conditions, exclus du calcul de la surface.

Unité foncière : l'unité foncière est constituée de l'ensemble des parcelles cadastrales contiguës qui appartiennent au même propriétaire ou à la même indivision.
L'unité foncière est la seule notion retenue pour l'application du règlement du PLU.

Voirie : les voies ouvertes à la circulation générale (affectées à la circulation publique) correspondent aux voies publiques ou privées permettant de relier entre eux les différents quartiers de la Commune. Elles se distinguent des voies dites de desserte, dont l'objet est la

liaison entre la voirie ouverte à la circulation générale et une opération déterminée. Il doit se référer au règlement de voirie annexé au présent règlement.

Définitions tirées du document « Construire à Belle-Ile » réalisé par le CAUE du Morbihan

Allège : mur d'appui compris entre une baie et le sol

Appareillage : Manière d'assembler les pierres pour la constitution d'un mur, d'une voûte, d'un arc, d'un linteau…

Appentis : Corps de bâtiment appuyé sur un bâtiment principal couvert par un toit à une seule pente dont le faîte s'appuie soit sur le pignon, soit sur le haut du mur de long pan à la hauteur de la rive d'égout.

Arbalétrier : Elément d'une ferme qui suit l'inclinaison du toit depuis le faîtage (ou il est assemblé au poinçon) jusqu'à la panne sablière. L'albalétrier supporte les pannes intermédiaires.

Arêtier : Pièce de charpente ou partie de la couverture qui se situe à l'angle saillant de la rencontre de deux rampants de toit (lorsque l'arrêtier est horizontal ou vertical de la bordure d'un mur, délimité ici par une engravure dans l'enduit servant à séparer deux couleurs d'enduit.

Bandeau : Elément continu horizontal ou vertical de la bordure d'un mur, délimité ici par une engravure dans l'enduit servant à séparer deux couleurs d'enduit.

Chanfrein : Surface plane oblique obtenue en abattant l'angle vif d'une pierre (ou de couronnement d'une souche).

Chevronnière : Partie haute d'un mur pignon, dépassant le plan de toiture et recouvrant l'extrémité de celle-ci.

Chien assis : Sorte de lucarne assez rare dont la pente de toit est à l'inverse de celle du rampant principal sur lequel elle s'appuie. On emploie improprement ce terme pour désigner la lucarne rampante, dont la pente est dans le prolongement du rampant principal mais d'inclinaison plus faible.

Contre butée : Etai ou partie de mur destiné à absorber les poussées latérales d'un arc ou d'une voûte.

Corbelet : pierre, pièce de bois ou de béton en saillie sur le parement d'un mur et généralement situé à la partie basse des chevronnières en prolongement de la corniche (on dit aussi quelquefois « crossette »).

Corniche : Moulure horizontale située en partie haute d'un mur et en saillie sur celui-ci. La corniche est destinée à éloigner l'eau de ruissellement du parement de mer qu'elle courronne.

Echiffre : Un mur d'échiffre est celui dont la partie supérieure supporte les marches ou le limon d'un escalier.

Faîtage : ligne horizontale formée par la section saillante de deux plans de toiture inclinés. Anthithèse : chêneau encaissé.

Ferme : Assemblage triangulé de pièces de charpente, situé dans un plan parallèle aux pignons et destiné à soutenir la toiture.

Jouée (ou joue) : Chacun des plans verticaux de forme triangulaire formant le côté d'une lucarne.

Linteau : Pièce de bois, de pierre, de béton armé, de métal etc… ou ensemble appareillé de pierres ou de briques couvrant la partie supérieure d'une baie et reportant les charges supérieures sur les piedroits latéraux.

Listel : Petite moulure plate en saillie sur un plan.

Longère : Bâtiment ou ensemble de bâtiments sensiblement de même importance accolés les uns aux autres et formant un tout orienté suivant une même direction.

Long pan : Se dit du mur plan d'un bâtiment, qui est couronné par la rive d'égoût horizontale d'un rampant de toiture (par opposition à mur pignon).

Mat pignon : Souche ou fausse souche de cheminée terminant la partie haute des pignons à Belle-Ile.

Mitron : Conduit en poterie tronconique prolongeant les conduits de fumée hors des souches.

Noue : Le contraire de l'arêtier.

Panne : Pièce de bois (de section 8cm x 22 cm actuellement) placée horizontalement sur les arbalétriers de ferme à des intervalles égaux et destinée à supporter les chevrons ; Panne faîtière : celle qui se trouve sous le faîtage. Panne Sablière : celle qui se repose sur le mur de long pan.

Petit bois : Baguette de bois ou de métal verticale ou horizontale servant à subdiviser les vitres des vantaux des fenêtres ou de portes.

Piedroit : Ensemble du support latéral du linteau d'une haie.

Pierres sèches : Se dit d'un appareillage dont les éléments, pierres, briques ou autres, sont simplement assemblés par empilage et juxtaposition sans l'adjonction d'un mortier.

Rampant : Plan incliné d'une toiture.

Refend : Mur porteur intermédiaire destiné à soulager ou recouper les poutres ou solives de grande portée.

Rive : Limite d'un versant de toit tant en pignon qu'en long pan. La limite basse horizontale d'un rampant de toit se nomme rive d'égout ou plus simplement égoût de toiture.

Solin : Couvre-joint de mortier ou de zinc etc…ou saillie de pierre à la jonction d'un toit ou d'un mur (ou d'une souche de cheminée), destiné à assurer l'étanchéité.

Tableau : Côté vertical d'une embrasure.

Ton : Couleur (ne pas confondre avec valeur)

Tuileau : Elément de tuile.

Valeur : Degré de clair ou de foncé d'une couleur ou d'une ombre.

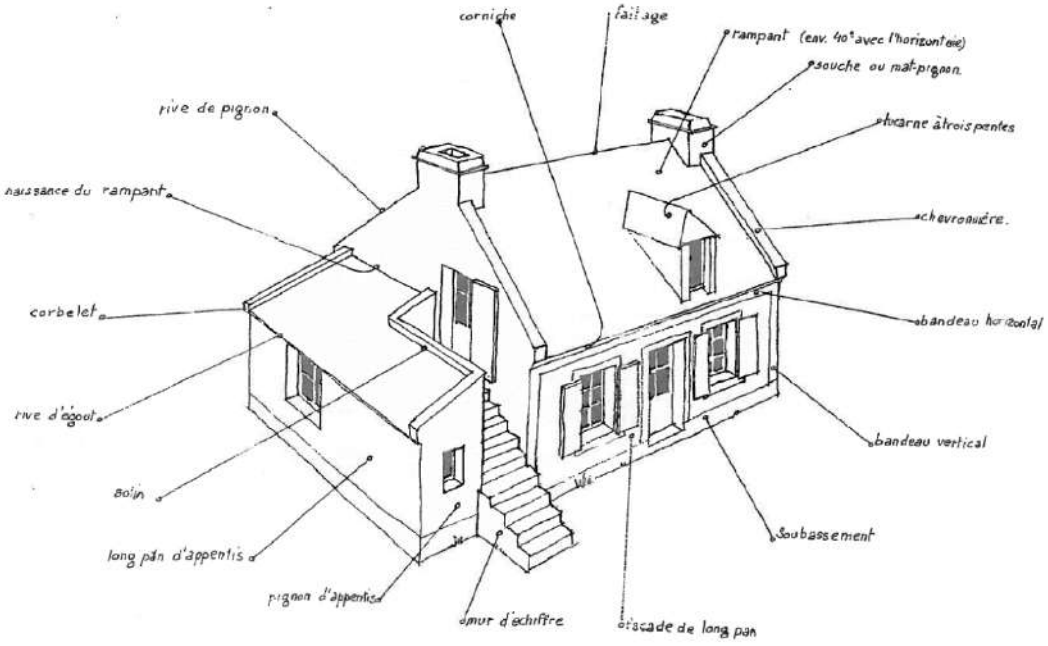
corniche
faîtage
rampant (env. 40° avec l'horizontale)
souche ou mat-pignon
rive de pignon
lucarne à trois pentes
naissance du rampant
chevronnière
corbelet
bandeau horizontal
rive d'égout
bandeau vertical
soin
soubassement
long pan d'appentis
pignon d'appentis
mur d'échiffre
arcade de long pan

CHAPITRE N°2 : DEFINITIONS DES DESTINATIONS DES CONSTRUCTIONS

HABITATION	
Logement	Constructions destinées au logement principal, secondaire ou occasionnel des ménages à l'exclusion des hébergements couverts par la sous-destination « Hébergement »
Hébergement	Constructions destinées à l'hébergement dans des résidences ou foyers avec service. Cette sous-destination recouvre notamment les maisons de retraite, les résidences universitaires, les foyers de travailleurs et les résidences autonomie.
Habitat Léger Permanent	Résidences démontables, constituant l'habitat permanent de leurs utilisateurs, destinées à être occupées à titre de résidence principale au moins huit mois par an. Il s'agit d'installations sans fondation disposant d'équipements intérieurs ou extérieurs et pouvant être autonomes vis-à-vis des réseaux publics.
COMMERCE ET ACTIVITE DE SERVICE	
Artisanat et commerce de détail	Constructions destinées à la présentation et vente de bien directe à une clientèle ainsi que les constructions artisanales destinées à la vente de biens ou services.
Restauration	Constructions destinées à la restauration ouverte à la vente directe pour une clientèle commerciale.
Commerce de gros	Constructions destinées à la présentation et à la vente de biens pour une clientèle professionnelle.
Activités de services où s'effectue l'accueil d'une clientèle	Constructions destinées à l'accueil d'une clientèle pour la conclusion directe de contrat de vente de services ou de prestations de services et accessoirement la présentation de biens.
Hébergement hôtelier	Constructions destinées à l'hébergement temporaire de courte ou moyenne durée proposant un service commercial.
Camping et hôtellerie de plein-air	Terrains dont la mise à disposition des touristes est commercialisée sous forme d'emplacements nus permettant l'installation d'une tente ou d'une caravane notamment, ou d'emplacements équipés d'une Résidence Mobile de Loisirs (RML) ou d'un Habitat Léger de Loisirs (HLL).
Aire naturelle de camping	Terrains dont la mise à disposition des touristes est commercialisée sous forme d'emplacements nus permettant l'installation d'une tente, d'une caravane et/ou d'autocaravanes.
Cinéma	Construction répondant à la définition d'établissement de spectacles cinématographique accueillant une clientèle commerciale.

EQUIPEMENTS D'INTERET COLLECTIF ET SERVICES PUBLICS	
Locaux et bureaux accueillant du public des administrations publiques et assimilés	Constructions destinées à assurer une mission de service public. Ces constructions peuvent être fermées au public ou ne prévoir qu'un accueil limité du public. Cette sous-destination comprend notamment les constructions de l'Etat, des collectivités territoriales, de leurs groupements ainsi que les constructions des autres personnes morales investies d'une mission de service public.
Locaux techniques et industriels des administrations publiques et assimilés	Constructions des équipements collectifs de nature technique ou industrielle. Cette sous-destination comprend notamment les constructions techniques nécessaires au fonctionnement des services publics, les constructions techniques conçues spécialement pour le fonctionnement de réseaux ou de services urbaines, les constructions industrielles concourant à la production d'énergie.
Etablissements d'enseignement, de santé et d'action sociale	Les équipements d'intérêts collectifs destinés à l'enseignement ainsi que les établissements destinés à la petite enfance, les équipements d'intérêts collectifs hospitaliers, les équipements collectifs accueillant des services sociaux, d'assistance, d'orientation et autres services similaires.
Salles d'art et de spectacles	Les constructions destinées aux activités créatives, artistiques et de spectacle, musées et autres activités culturelles d'intérêt collectif.
Equipements sportifs	Equipements d'intérêts collectifs destinées à l'exercice d'une activité sportive. Cette sous-destination comprend notamment les stades, les gymnases ainsi que les piscines ouvertes au public.
Autres équipements recevant du public	Equipements collectifs destinés à accueillir du public afin de satisfaire un besoin collectif ne répondant à aucune autre sous-destination définie au sein de la destination « Equipement d'intérêt collectif et services publics ». Cette sous-destination recouvre notamment les lieux de culte, les salles polyvalentes, les aires d'accueil des gens du voyage.
AUTRES ACTIVITES DES SECTEURS SECONDAIRE OU TERTIAIRE	
Industrie	Constructions destinées à l'activité extractive et manufacturière du secteur primaire, les constructions destinées à l'activité industrielle du secteur secondaire ainsi que les constructions artisanales du secteur de la construction ou de l'industrie. Cette sous-destination recouvre notamment les activités de production, de construction ou de réparation susceptibles de générer des nuisances.
Entrepôt	Constructions destinées au stockage des biens ou à la logistique.
Bureau	Constructions destinées aux activités de direction et de gestion des entreprises des secteurs primaires, secondaires et tertiaires.

Centre de congrès et d'exposition	Constructions destinées à l'évènementiel polyvalent, l'organisation de salons et forums à titre payant.
EXPLOITATION AGRICOLE ET FORESTIERE	
Exploitation agricole	Constructions destinées à l'exercice d'une activité agricole ou pastorale. Cette sous-destination recouvre notamment les constructions destinées au logement du matériel, des animaux et des récoltes.
Exploitation forestière	Constructions et entrepôts notamment de stockage du bois, des véhicules et des machines permettant l'exploitation forestière.
AUTRES OCCUPATIONS ET UTILISATIONS DU SOL	
Les coopératives d'utilisation de matériel agricole agréées.	Constructions et installations destinées au fonctionnement de la CUMA.
Les locaux et installations de diversification de l'activité agricole	Constructions et installations destinées aux activités de diversification de l'activité agricole. Sont notamment compris dans cette sous-destination, les locaux de transformation et de vente directe.
Le camping à la ferme	Terrain aménagé situé sur une exploitation agricole en activité, à proximité immédiate de l'habitation de l'exploitant. Il peut comprendre 6 emplacements ou 20 campeurs sous tentes et peut accueillir des tentes, des caravanes et des autocaravanes.
Le changement de destination	Changement de la destination de la construction
La reconstruction à l'identique	
Les piscines	
Les affouillements et exhaussements de sol	Il s'agit des affouillements et exhaussements du sol dont la hauteur, s'il s'agit d'un exhaussement, ou la profondeur dans le cas d'un affouillement, excède deux mètres et qui portent sur une superficie supérieure ou égale à 100 m².
Les carrières	Cette destination comprend le site d'exploitation en lui-même mais également toutes les installations et constructions nécessaires à cette exploitation.
Les déchets de toute nature, le stockage de ferrailles et matériaux de démolition ou de récupération	-
Le stationnement isolé de caravanes	-

CHAPITRE N°3 : GUIDE D'APPLICATION DE L'ARTICLE R111-2 DU CU POUR ASSURER LA SECURITE DES PERSONNES ET DES BIENS EXPOSES AU RISQUE DE SUBMERSION MARINE

1. Rappels sur l'article R111-2 du Code de l'Urbanisme

Concernant les projets d'urbanisme, l'article R111-2 du Code de l'Urbanisme précise que : « le projet peut être refusé ou n'être accepté que sous réserve de l'observation de prescriptions spéciales s'il est de nature à porter atteinte à la salubrité ou à la sécurité publique du fait de sa situation, de ses caractéristiques, de son importance ou de son implantation à proximité d'autres installations ».
Cet article vise à réglementer des projets portant notamment atteinte à la sécurité publique du fait même de leur situation en zone exposée à un risque. Relèvent de la sécurité publique toutes les mesures et tous les moyens mis en œuvre par l'Etat et les maires pour assurer la sécurité des personnes et des biens. Sont concernés les projets de construction, d'aménagement, d'installations et de travaux faisant l'objet d'un permis de construire, d'un permis d'aménager ou d'une déclaration préalable ainsi que toutes autres utilisations du sol régies par le Code de l'urbanisme.

Les submersions marines sont de nature à mettre en péril la sécurité des personnes présentes dans les zones exposées et à provoquer des dommages aux biens qui s'y trouvent. Tout projet d'urbanisme dans ces zones soulève donc la question de la sécurité des personnes et de la protection des biens et mérite en conséquence une attention particulière des services en charge de l'instruction des projets, sur la base de cet article R111-2.

2. Objectifs du guide et contenu

Le présent guide constitue un outil d'aide à la décision pour l'instruction des projets présentés au titre de l'urbanisme sur les territoires exposés au risque de submersion marine. Il s'appuie sur les dispositions de l'article R111-2 du Code de l'urbanisme et de la circulaire du 7 avril 2010 relative aux mesures à prendre en compte suite à la tempête Xynthia du 28 février 2010.

Ce guide est applicable à tout territoire exposé au risque de submersion marine, excepté lorsqu'il est couvert par un plan de prévention des risques littoraux (PPRL) approuvé. Lorsque, postérieurement à l'approbation du PPRL, des connaissances nouvelles sont disponibles sur l'exposition au risque du territoire, les éléments de ce guide sont de nouveau pris en considération.

Les préconisations de ce guide diffèrent en fonction du projet concerné et du niveau d'aléa auquel ce projet est exposé

Le guide expoose des principes fondamentaux (précisés au 4. ci-dessous), applicables à tous les projets, et fournit en annexe des exemples d'application de ces principes à quelques cas fréquemment rencontrés en urbanisme. Ces grilles ont simplement valeur d'exemple et ne sont pas exhaustives. Elles peuvent faire l'objet d'adaptations et de compléments dans le respect des principes fondamentaux du guide. Dans la plupart des situations rencontrées en zone submersible, le guide propose l'interdiction du projet ou son autorisation, le cas échéant assortie de prescriptions.

Les préconisations de ce guide ne préjugent pas des autres réglementations applicables

3. Modalités d'application

Pour l'application des principes fondamentaux exposés au 4. ci-dessous et des exemples d'application, il convient de se reporter aux cartes des zones exposées au risque de submersion marine portées à la connaissance des communes en application de l'article L121-2 du Code de l'urbanisme, ainsi qu'à leurs notices techniques d'accompagnement. Y sont notamment définies et représentées les zones d'aléa fort, les zones d'aléa moyen, les zones de dissipation d'énergie à l'arrière des systèmes de protection connus et les zones d'aléa lié au changement climatique.

4. Les principes fondamentaux

L'application de l'article R111-2 doit conduire à ne pas augmenter la vulnérabilité des personnes et des biens publics et privés, ni leur exposition au risque. L'instruction des projets d'urbanisme doit se faire en respectant notamment les principes suivants :

1. Dans les zones submersibles, quel que soit le niveau d'aléa ou d'urbanisation, peuvent être autorisées :

- les travaux de mise aux normes, d'entretien, de réfection ou les travaux de réduction de la vulnérabilité, c'est-à-dire les travaux visant à adapter le bâtiment à sa situation en zone inondable comme par exemple la mise en place de batardeaux, la création d'accès pour permettre l'évacuation ;
- les projets d'infrastructures nécessaires au fonctionnement des services publics et dont l'implantation n'est pas réalisable ailleurs ;
- les projets de bâtiments d'activité dont l'implantation n'est pas possible ailleurs, notamment ceux nécessitant la proximité immédiate de la mer.

2. Dans les zones de dissipation d'énergie à l'arrière des systèmes de protection connus ou d'aléa fort, les projets conduisant à augmenter le nombre de personnes exposées ne sont pas autorisés, exceptés les projets d'extension de bâtiments existants autres que les établissements « sensibles » visés au 3. ci-dessous. Dans les dents creuses soumises à ces

niveaux d'aléa, les projets ne conduisant pas à augmenter le nombre de résidents peuvent faire l'objet d'un examen particulier, hors établissements sensibles.

3. Les projets d'établissements « sensibles » ne sont pas autorisés lorsqu'ils conduisent à implanter ces établissements ou toutes leurs voies d'accès en zone inondable dans les zones de dissipation d'énergie à l'arrière des systèmes de protection connus et dans les zones d'aléa fort ou d'aléa moyen. Sont concernés les établissements difficilement évacuables et les établissements stratégiques ou indispensables à la gestion de crise.

4. Dans les zones submersibles, quel que soit le niveau d'aléa, les projets de sous-sols et de parkings souterrains sont interdits, à l'exception des projets de parkings collectifs, en zone d'aléa futur uniquement et lorsque les deux conditions suivantes sont réunies : tous les accès au parking sont implantés à la cote NMR 2100 [NMR (NMC + 0,20 m) + 0,40 m] + 0,20 m et l'étanchéité des points d'infiltration est de nature à empêcher tout remplissage du parking.

5. Lorsqu'un projet est autorisé en zone submersible, il peut être assorti de prescriptions proportionnées au niveau d'aléa concerné et à la nature du projet proposé. Ces prescriptions doivent permettre de réduire la vulnérabilité de personnes résidentes, des personnes liées aux activités et des biens. Les mesures sur le bâti peuvent par exemple concerner :

- le positionnement à une cote minimale du premier niveau de plancher (en privilégiant les vides-sanitaires) ou des pièces de sommeil ;
- la création d'une zone refuge située à une cote minimale et permettant l'évacuation en cas de submersion ;
- …

Note : Il est recommandé d'informer le pétitionnaire de dispositions constructives permettant de réduire la vulnérabilité des bâtiments ou d'éviter de causer des dommages à l'environnement, comme par exemple les mesures suivantes (liste non limitative et à adapter en fonction de la nature du projet) :

- des mesures constructives analogues à celles visées ci-dessus pour les prescriptions sur le bâti ;
- absence de volets électriques sur les ouvrants réalisés pour l'évacuation par les services de secours (ouverture manuelle demandée) ;
- surélévation des équipements tels que compteur électrique, réseaux électriques, chaudière, cuve à fioul ;
- utilisation de matériaux et de revêtements hydrofuges ou peu sensibles à l'eau pour les sols et les murs ;
- installation de clapets anti-retour sur les réseaux d'eaux usées ;
- concernant les stockages de polluants : le stockage en récipients ou citernes étanches, l'assujettissement des récipients à une fondation ou à une structure fixe, l'ancrage des citernes enterrées et le lestage ou l'arrimage des autres types de citernes, le débouché de tuyaux d'évent à une cote hors d'eau.
- …

Ces mesures de réduction de la vulnérabilité pourront par exemple être fournies dans une fiche accompagnant l'arrêté d'autorisation du projet.

5. Exemples d'application de l'article R111-2

Annexe – Exemples d'application de l'article R111-2

La présente annexe propose des exemples d'application de l'article R111-2 à quelques types de projets fréquemment rencontrés en urbanisme. Dans la suite du document :

- les dispositions suivantes, formulées sous la forme de prescriptions ou d'informations, traduisent les suggestions d'aménagement exposées ci-après :
  - *1er niveau plancher à NMR* (ou NMR 2100*)*: placer le premier niveau de plancher à 0,20 m (marge de 0,20 m pour la prise en compte des incertitudes sur le bâti) au-dessus du niveau marin de référence, en créant un vide sanitaire ;
  - *pièces de sommeil à NMR* (ou NMR 2100*)* : placer les planchers de toutes les pièces de sommeil à 0,20 m (marge de 0,20 m pour la prise en compte des incertitudes sur le bâti) au-dessus du niveau marin de référence, en prévoyant un accès possible des secours pour l'évacuation par les services de secours (balcon, fenêtre,...) ;
  - *niveau refuge à NMR* (ou NMR 2100*)* : créer un niveau refuge positionné à 0,20 m (marge de 0,20 m pour la prise en compte des incertitudes sur le bâti) au-dessus du niveau marin de référence, facile d'accès pour les occupants et permettant l'évacuation par les services de secours (balcon, fenêtre,...) ; ce niveau refuge doit être correctement dimensionné pour abriter l'ensemble des personnes occupant habituellement le bâtiment ;
- les zones de dissipation de l'énergie à l'arrière des systèmes de protection connus désignent les zones de sur-aléa engendrées par la rupture de ces systèmes. Elles sont matérialisées sur les cartes par une bande forfaitaire de 100 mètres.

* La cote du niveau marin de référence (NMR) correspond au niveau marin centennal (NMC) du SHOM, auquel est ajouté une marge de 0,20 m constituant la première étape de prise en compte du changement climatique (non pris en compte dans le niveau marin centennal du SHOM).

* La cote du niveau marin de référence 2100 (NMR 2100) correspond au niveau marin centennal (NMC) du SHOM, auquel est ajouté une marge de 0,60 m pour la prise en compte de l'impact de réchauffement climatique sur le niveau de la mer à l'horizon 2100 (élévation correspondant aux hypothèses pessimistes de l'Observatoire national sur les effets du réchauffement climatique).

Projet	Zone d'aléa fort et zone de dissipation d'énergie	Zone d'aléa moyen	Zone d'aléa liée au changement climatique
Création d'une habitation individuelle ou collective	Le projet ne doit pas être autorisé, car il conduirait à augmenter le nombre de personnes exposées sur un lieu d'hébergement non existant.	Le projet peut être autorisé compte tenu du niveau d'aléa en présence et moyennant la mise en œuvre de dispositions constructives adaptées permettant de protéger les personnes et les biens exposés. On pourra ainsi prescrire un 1er niveau de plancher à la cote NMR + 0,20 m et informer le pétitionnaire des mesures de réduction de la vulnérabilité.	Le projet peut être autorisé compte tenu du niveau d'aléa à venir. Le pétitionnaire pourra également être informé de dispositions constructives lui permettant de s'adapter aux effets du changement climatique. On pourra ainsi l'informer de l'intérêt de placer le 1er niveau de plancher ou des pièces de sommeil à la cote NMR 2100 (NMR + 0,40 m) + 0,20 m et des mesures de réduction de la vulnérabilité.
Extension d'une maison d'habitation	Le projet peut être autorisé, sous réserve que la surface d'extension ne soit pas trop importante et que le pétitionnaire respecte certaines dispositions constructives, afin de limiter l'exposition des personnes et de nouveaux biens sur un lieu d'hébergement existant.	Le projet peut être autorisé, compte tenu du niveau d'aléa en présence, sous réserve que le pétitionnaire respecte certaines dispositions constructives, afin de limiter l'exposition des personnes et de nouveaux biens sur un lieu d'hébergement existant.	
	Dans ces zones d'aléa, on pourra ainsi prescrire un 1er niveau de plancher à la cote NMR + 0,20 m (ou à défaut demander la création d'un niveau refuge à cette même cote, sauf si le bâtiment existant comporte déjà un niveau refuge accessible). On demandera également de ne pas placer de pièces de sommeil dans les pièces situées sous la cote NMR + 0,20 m, lorsque le 1er niveau de plancher n'atteint pas la cote NMR + 0,20 m. Enfin le pétitionnaire sera informé des mesures de réduction de la vulnérabilité.		

Projet	Zone d'aléa fort et zone de dissipation d'énergie	Zone d'aléa moyen	Zone d'aléa liée au changement climatique
Transformation d'une grange en maison d'habitation	Le projet ne doit pas être autorisé, car il conduirait à augmenter le nombre de personnes exposées sur un lieu d'hébergement non existant	Le projet peut être autorisé, compte tenu du niveau d'aléa en présence, et sous réserve que le pétitionnaire respecte certaines dispositions constructives, afin de limiter l'exposition des personnes et de nouveaux biens sur un nouveau lieu d'hébergement. On pourra ainsi prescrire un 1er niveau de plancher à la cote NMR + 0,20 m et informer le pétitionnaire des mesures de réduction de la vulnérabilité.	Le projet peut être autorisé compte tenu du niveau d'aléa à venir. Le pétitionnaire pourra également être informé de dispositions constructives lui permettant de s'adapter aux effets du changement climatique. On pourra ainsi l'informer de l'intérêt de placer le 1er niveau de plancher ou des pièces de sommeil à la cote NMR 2100 (NMR + 0,40 m) + 0,20 m et des mesures de réduction de la vulnérabilité.
Transformation d'une grange en garage individuel	Le projet peut être autorisé, car il ne conduit pas à augmenter le nombre de personnes exposées, ni (a priori) les biens exposés.		
Création d'un immeuble de bureau	Le projet ne doit pas être autorisé, car il conduirait à augmenter le nombre de personnes exposées sur leur lieu de travail et qu'il exposerait de nouveaux biens à un aléa fort.	Le projet peut être autorisé compte tenu du niveau d'aléa en présence et moyennant la mise en œuvre de dispositions constructives adaptées permettant de protéger les personnes sur un nouveau lieu de travail ainsi que les biens exposés. On pourra ainsi prescrire un 1er niveau de plancher à la cote NMR + 0,20 m et informer le pétitionnaire des mesures de réduction de la vulnérabilité.	Le projet peut être autorisé compte tenu du niveau d'aléa à venir. Le pétitionnaire pourra également être informé de dispositions constructives lui permettant de s'adapter aux effets du changement climatique. On pourra ainsi l'informer de l'intérêt de placer le 1er niveau de plancher à la cote NMR 2100 (NMR + 0,40 m) + 0,20 m (ou à défaut de créer un niveau refuge à cette cote) et des mesures de réduction de la vulnérabilité

Projet	Zone d'aléa fort et zone de dissipation d'énergie	Zone d'aléa moyen	Zone d'aléa liée au changement climatique
Transformation d'une grange en bureau	Le projet ne doit pas être autorisé, car il conduirait à augmenter le nombre de personnes exposées sur leur lieu de travail et il exposerait de nouveaux biens à un aléa fort.	Le projet peut être autorisé compte tenu du niveau d'aléa en présence et moyennant la mise en œuvre de dispositions constructives adaptées permettant de protéger les personnes sur leur nouveau lieu de travail ainsi que les biens exposés. On pourra ainsi prescrire un 1er niveau de plancher à la cote NMR + 0,20 m (ou à défaut de créer un niveau refuge à cette cote) et informer le pétitionnaire des mesures de réduction de la vulnérabilité.	Le projet peut être autorisé compte tenu du niveau d'aléa à venir. Le pétitionnaire pourra également être informé de dispositions constructives lui permettant de s'adapter aux effets du changement climatique. On pourra ainsi l'informer de l'intérêt de placer le 1er niveau de plancher à la cote NMR 2100 (NMR + 0,40 m) + 0,20 m (ou à défaut de créer un niveau refuge à cette cote) et des mesures de réduction de la vulnérabilité
Création d'une crèche ou d'une maison de retraite	Le projet ne doit pas être autorisé, compte tenu du fait qu'il conduirait à augmenter le nombre de personnes exposées sur leur lieu d'activité ou de vie, et qu'il s'agit d'une population particulièrement sensible (enfants et personnes âgées), à mobilité réduite et difficilement évacuable.		
Création d'une caserne de pompier	Le projet ne doit pas être autorisé, car il concerne un bâtiment stratégique pour la gestion de crise, dont l'implantation en zone inondable serait préjudiciable au bon fonctionnement de l'établissement en cas d'inondation.		
Extension d'un centre d'hébergement pour adultes handicapés avec augmentation de la capacité d'accueil	Le projet ne doit pas être autorisé, compte tenu du fait qu'il conduirait à augmenter le nombre de personnes exposées sur leur lieu de vie, et qu'il s'agit d'une population particulièrement sensible, difficilement évacuable.		Le projet peut être autorisé avec prescription, sous réserve qu'il existe des moyens d'accès à l'établissement non situés en zone submersible. En effet, compte tenu du niveau d'aléa à venir, la mise en œuvre de dispositions constructives adaptées doit permettre de protéger cette population sensible sur leur lieu de vie ainsi que les biens exposés, dans une logique d'adaptation aux effets du changement climatique. On pourra ainsi prescrire un 1er niveau de plancher à la cote NMR 2100 (NMR + 0,40 m) + 0,20 m et informer le pétitionnaire des mesures de réduction de la vulnérabilité.

Projet	Zone d'aléa fort et zone de dissipation d'énergie	Zone d'aléa moyen	Zone d'aléa liée au changement climatique
Extension d'une maison de retraite par ajout d'une salle de loisir possédant une mezzanine à la cote NMR + 0,20 m accessible par des personnes à mobilité réduite	Le projet peut être autorisé lorsque le bâtiment existant n'est pas de nature à assurer la protection des résidents en cas de submersion. En effet cette mezzanine, si elle est facilement accessible, peut constituer une zone refuge pour les personnes âgées. Le pétitionnaire sera informé des mesures de réduction de la vulnérabilité.	Le projet peut être autorisé compte tenu du niveau d'aléa en présence et moyennant la mise en œuvre de dispositions constructives adaptées permettant de protéger les personnes sur un nouveau lieu d'activité ainsi que les biens exposés. On pourra ainsi prescrire un 1er niveau de plancher à la cote NMR 2100 + 0,20 m et informer le pétitionnaire des mesures de réduction de la vulnérabilité. La cote NMR 2100 (NMR + 0,40 m) + 0,20 m (et non NMR + 0,20 m habituellement retenue en zone d'aléa moyen) permet de se préparer au changement climatique pour ces établissements particulièrement sensibles.	Le projet peut être autorisé compte tenu du niveau d'aléa à venir et moyennant la mise en œuvre de dispositions constructives adaptées permettant de protéger des personnes sur un nouveau lieu d'activité, ainsi que les biens exposés, dans une logique d'adaptation aux effets du changement climatique. On pourra ainsi prescrire un 1er niveau de plancher à la cote NMR 2100 (NMR + 0,40 m) + 0,20 m et informer le pétitionnaire des mesures de réduction de la vulnérabilité.
Extension d'une maison de retraite par ajout de locaux techniques	Le projet peut être autorisé, car il ne conduit pas à augmenter le nombre de personnes exposées. Le pétitionnaire sera informé des mesures de réduction de la vulnérabilité des nouveaux biens ainsi exposés.		
Transformation d'un pavillon en crèche	Le projet ne doit pas être autorisé, compte tenu du fait qu'il conduirait à augmenter le nombre de personnes exposées sur leur lieu de vie, et qu'il s'agit d'une population particulièrement sensible (enfants), difficilement évacuable en cas de crise		

Projet	Zone d'aléa fort et zone de dissipation d'énergie	Zone d'aléa moyen	Zone d'aléa liée au changement climatique
Création d'un hôtel	Le projet ne doit pas être autorisé, car il conduirait à augmenter le nombre de personnes exposées sur un lieu d'hébergement et qu'il exposerait de nouveaux biens à un aléa fort.	Le projet peut être autorisé, compte tenu du niveau d'aléa en présence, et sous réserve que le pétitionnaire respecte certaines dispositions constructives, afin de limiter l'exposition des personnes et de nouveaux biens sur un nouveau lieu d'hébergement. On pourra ainsi prescrire un 1er niveau de plancher à la cote NMR + 0,20 m et informer le pétitionnaire des mesures de réduction de la vulnérabilité.	Le projet peut être autorisé compte tenu du niveau d'aléa à venir. Le pétitionnaire pourra également être informé de dispositions constructives lui permettant de s'adapter aux effets du changement climatique. On pourra ainsi l'informer de l'intérêt de placer le 1er niveau de plancher à la cote NMR 2100 (NMR + 0,40 m) + 0,20 m (ou à défaut de créer un niveau refuge à cette même cote) et des mesures de réduction de la vulnérabilité
Transformation d'un commerce en un autre commerce (boulangerie, vêtement, ...)	Le projet peut être autorisé compte tenu du fait qu'il ne conduit pas à augmenter le nombre de personnes et de biens (a priori) déjà exposés On pourra tout de même informer le pétitionnaire de l'intérêt de placer le 1er niveau de plancher à la cote NMR + 0,20 m (ou à défaut de créer un niveau refuge à cette même cote) et des mesures de réduction de la vulnérabilité.		Le projet peut être autorisé compte tenu du niveau d'aléa à venir. Le pétitionnaire pourra également être informé de dispositions constructives lui permettant de s'adapter aux effets du changement climatique. Le pétitionnaire sera informé des mesures de réduction de la vulnérabilité
Mise en place de mobile home dans un camping / extension de la capacité d'un camping	Le projet ne doit pas être autorisé, car il conduirait à augmenter le nombre de personnes exposées sur un lieu d'hébergement et qu'il exposerait de nouveaux biens particulièrement sensibles à un aléa fort ou moyen.		Le projet peut être autorisé compte tenu du niveau d'aléa à venir. Le pétitionnaire pourra également être informé de dispositions constructives lui permettant de s'adapter aux effets du changement climatique. On pourra ainsi l'informer de l'intérêt de placer les voies d'accès hors d'eau et de créer une zone refuge à la cote NMR 2100 (NMR + 0,40 m) + 0,20 m lorsqu'il n'en existe pas.

Projet	Zone d'aléa fort et zone de dissipation d'énergie	Zone d'aléa moyen	Zone d'aléa liée au changement climatique
Aménagement de sanitaires et de douches dans un camping existant	Le projet peut être autorisé, car il ne conduit pas à augmenter le nombre de personnes exposées. Le pétitionnaire sera informé des mesures de réduction de la vulnérabilité des nouveaux biens ainsi exposés.		
Création d'un parking souterrain	Le projet ne doit pas être autorisé car il contribuerait à créer un lieu « piège » en cas de submersion (remplissage du parking), ce qui générerait un risque trop important de noyade pour les usagers piégés dans le parking ou dans leur véhicule.		Le projet peut être autorisé compte tenu du niveau d'aléa à venir et moyennant la mise en œuvre de dispositions constructives adaptées permettant de protéger des personnes exposées et leur véhicule, dans une logique d'adaptation aux effets du changement climatique. On pourra ainsi prescrire l'implantation des accès à la cote NMR 2100 (NMR + 0,40 m) + 0,20 m et l'étanchéité des points d'infiltration pour éviter un remplissage du parking. Le pétitionnaire sera également informé des mesures de réduction de la vulnérabilité
Création d'un parking aérien	Le projet peut être autorisé car il ne contribuerait pas à créer un lieu « piège » en cas de submersion.		
Implantation d'un transformateur électrique	Le projet peut être autorisé lorsque son implantation n'est pas possible ailleurs, afin de limiter l'implantation de nouveaux biens en zone submersible, notamment lorsqu'ils interviennent dans la continuité de services publics. Le pétitionnaire sera informé des mesures de réduction de la vulnérabilité des nouveaux biens ainsi exposés.		

6. Cartographie du risque de submersion marine

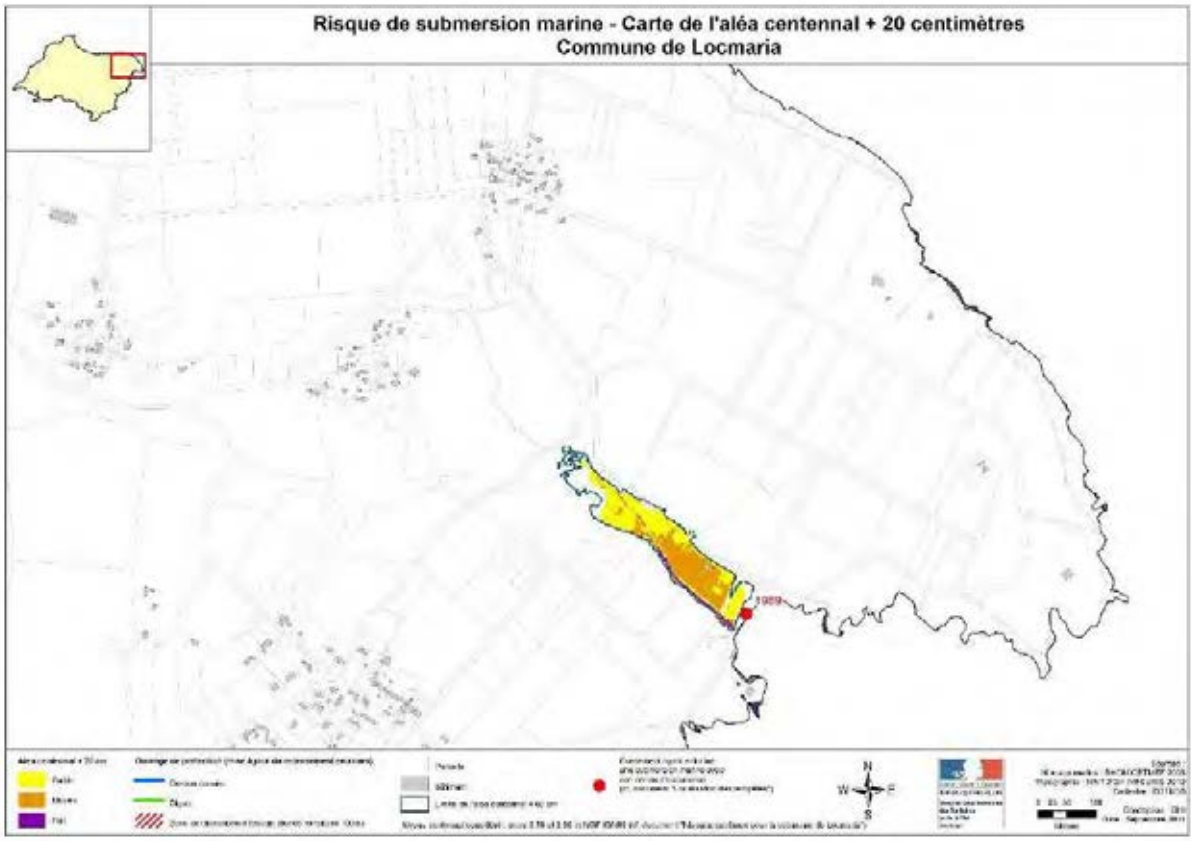

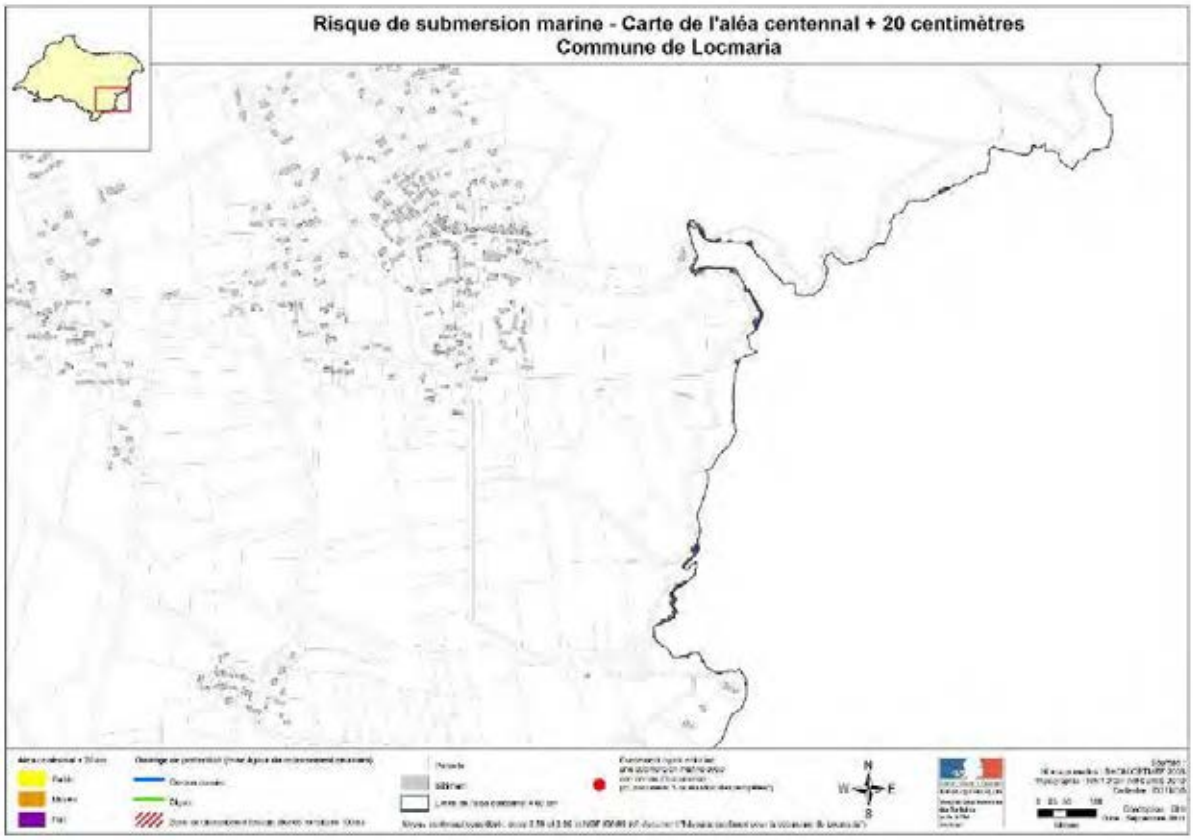

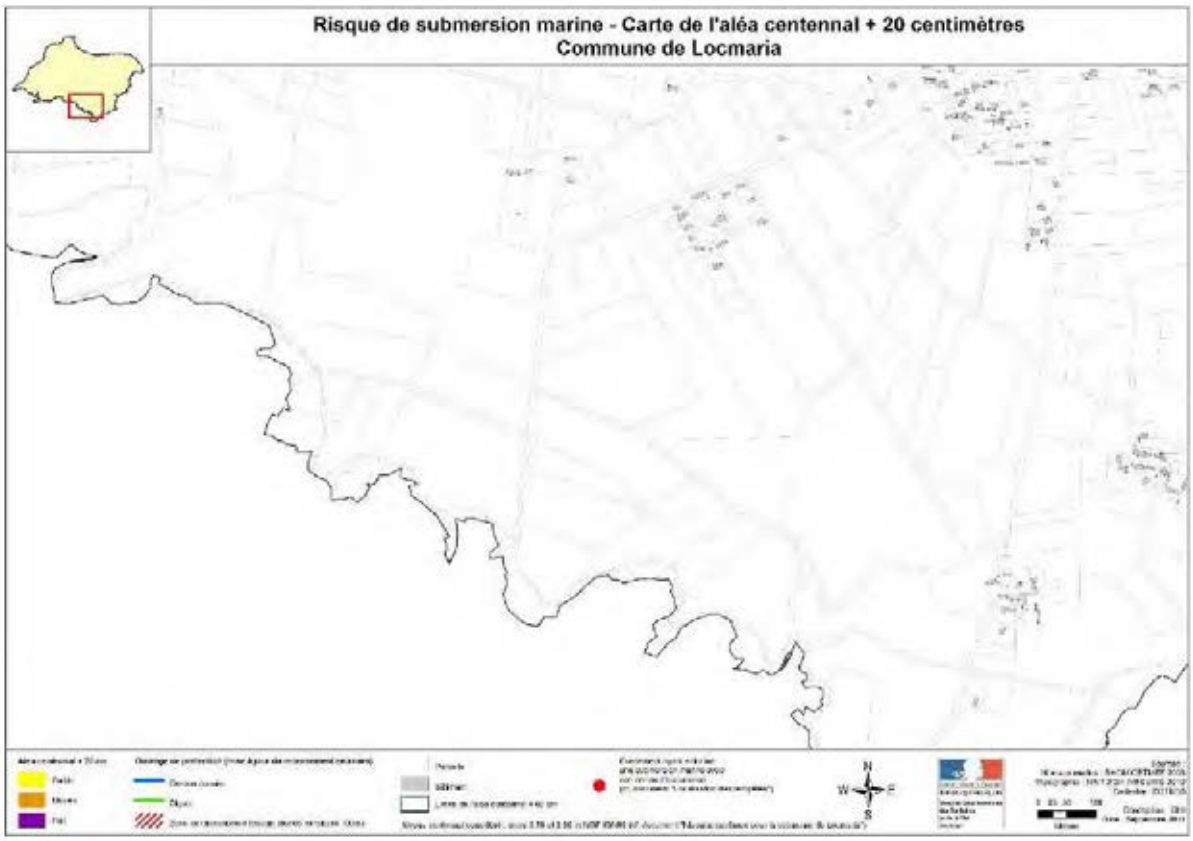
Risque de submersion marine - Carte de l'aléa centennal + 20 centimètres
Commune de Locmaria

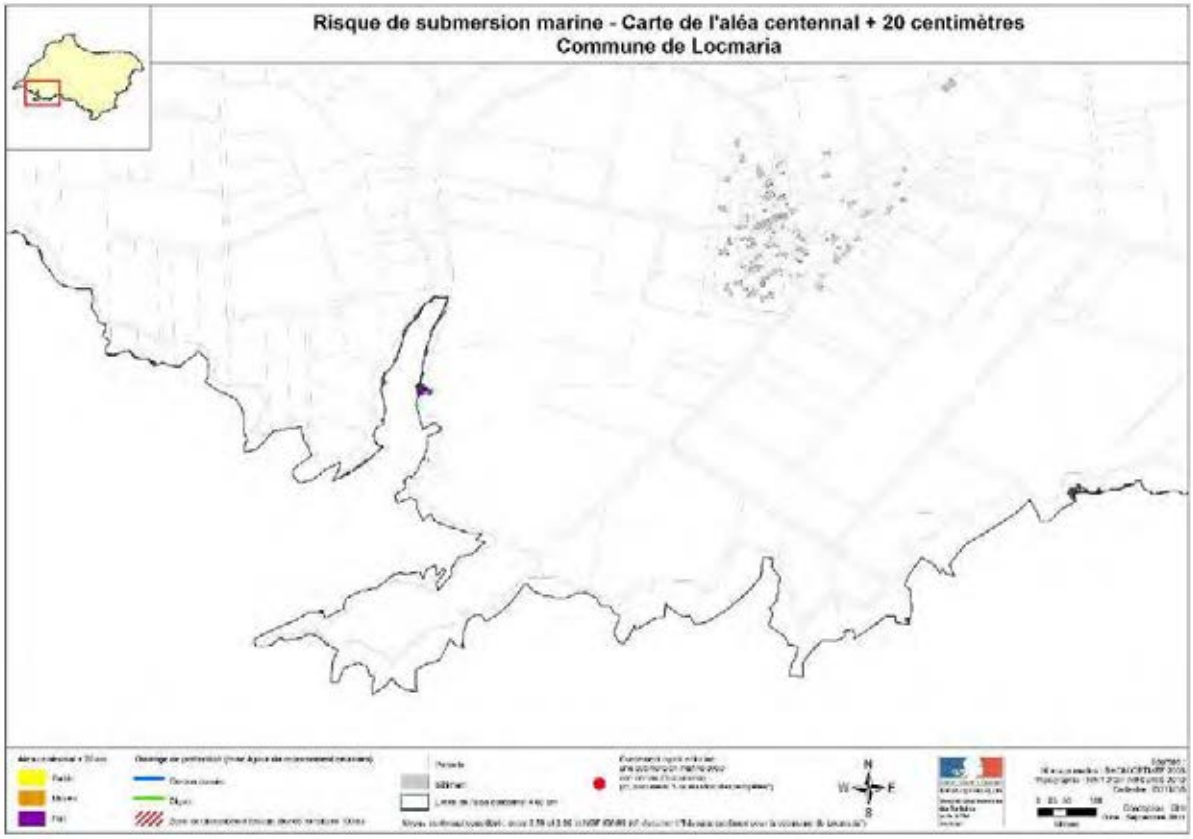
Risque de submersion marine - Carte de l'aléa centennal + 20 centimètres
Commune de Locmaria

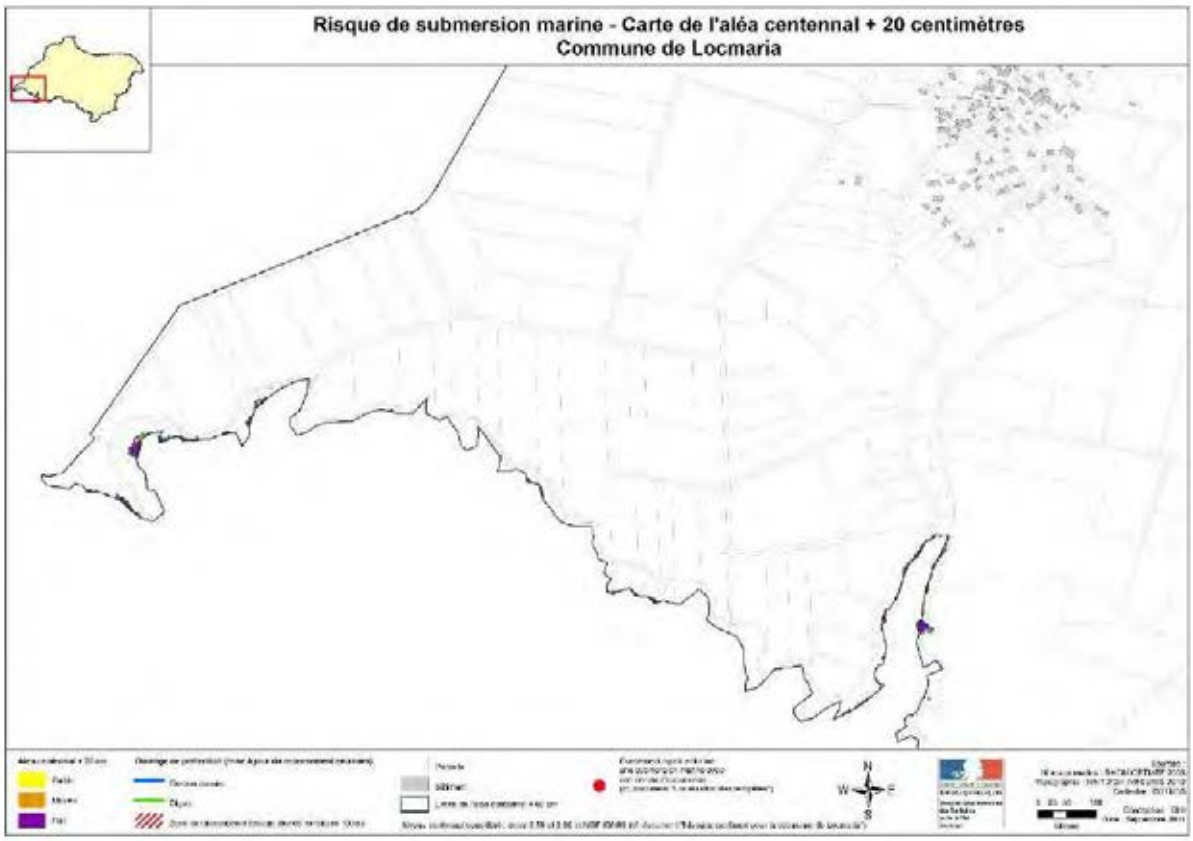
Risque de submersion marine - Carte de l'aléa centennal + 20 centimètres
Commune de Locmaria

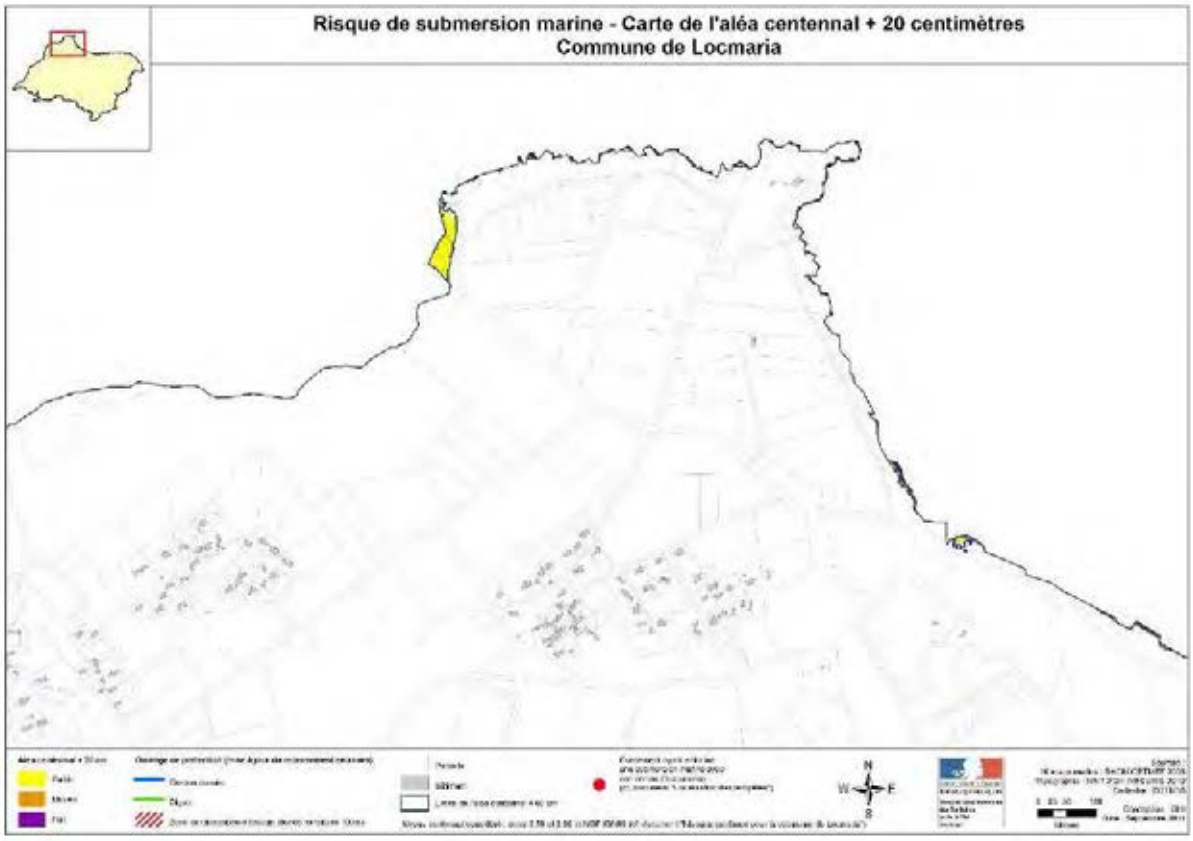
Risque de submersion marine - Carte de l'aléa centennal + 20 centimètres
Commune de Locmaria

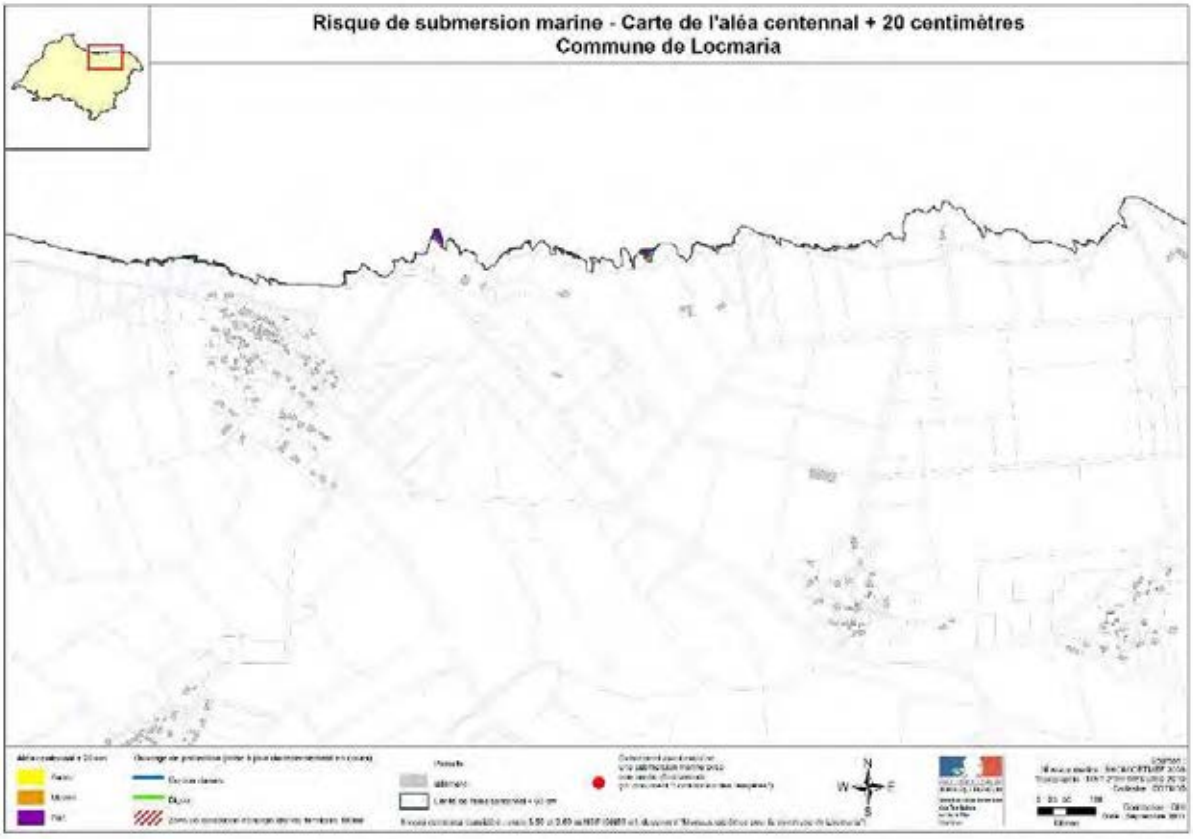
Risque de submersion marine - Carte de l'aléa centennal + 20 centimètres
Commune de Locmaria

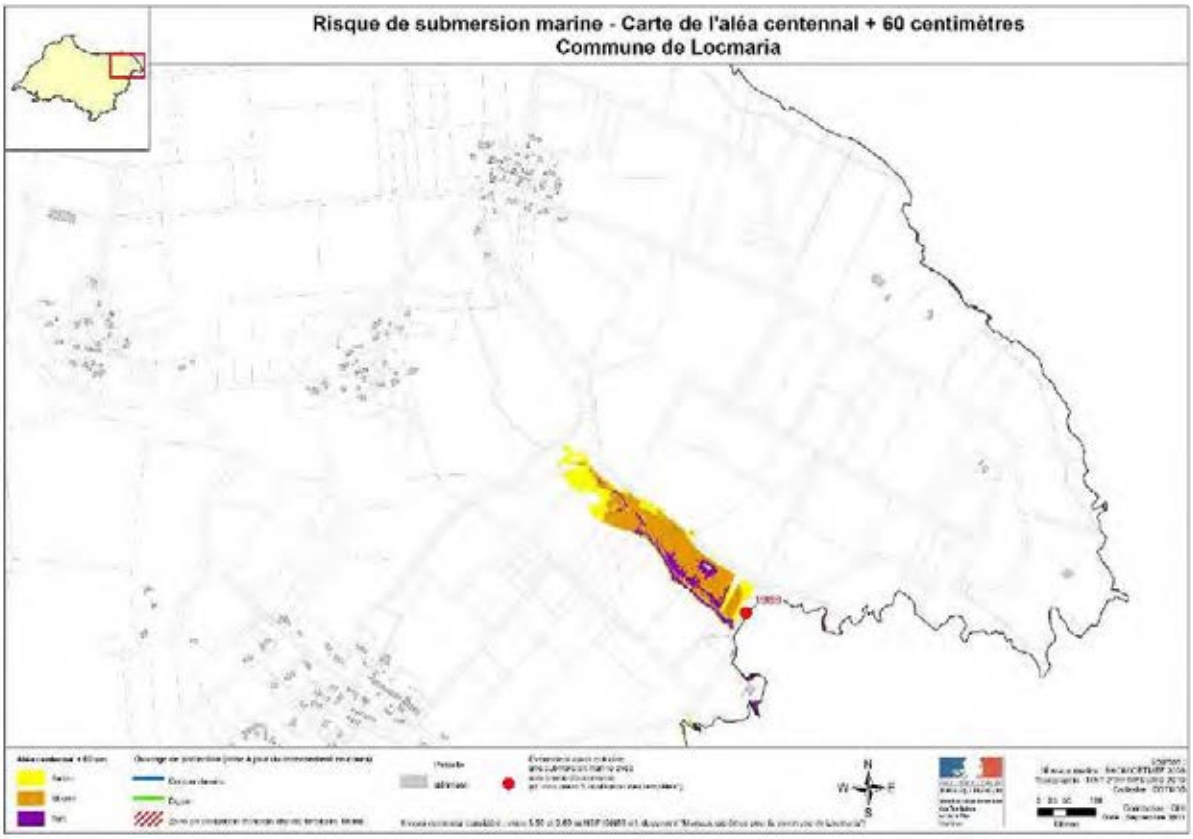
Risque de submersion marine - Carte de l'aléa centennal + 60 centimètres
Commune de Locmaria

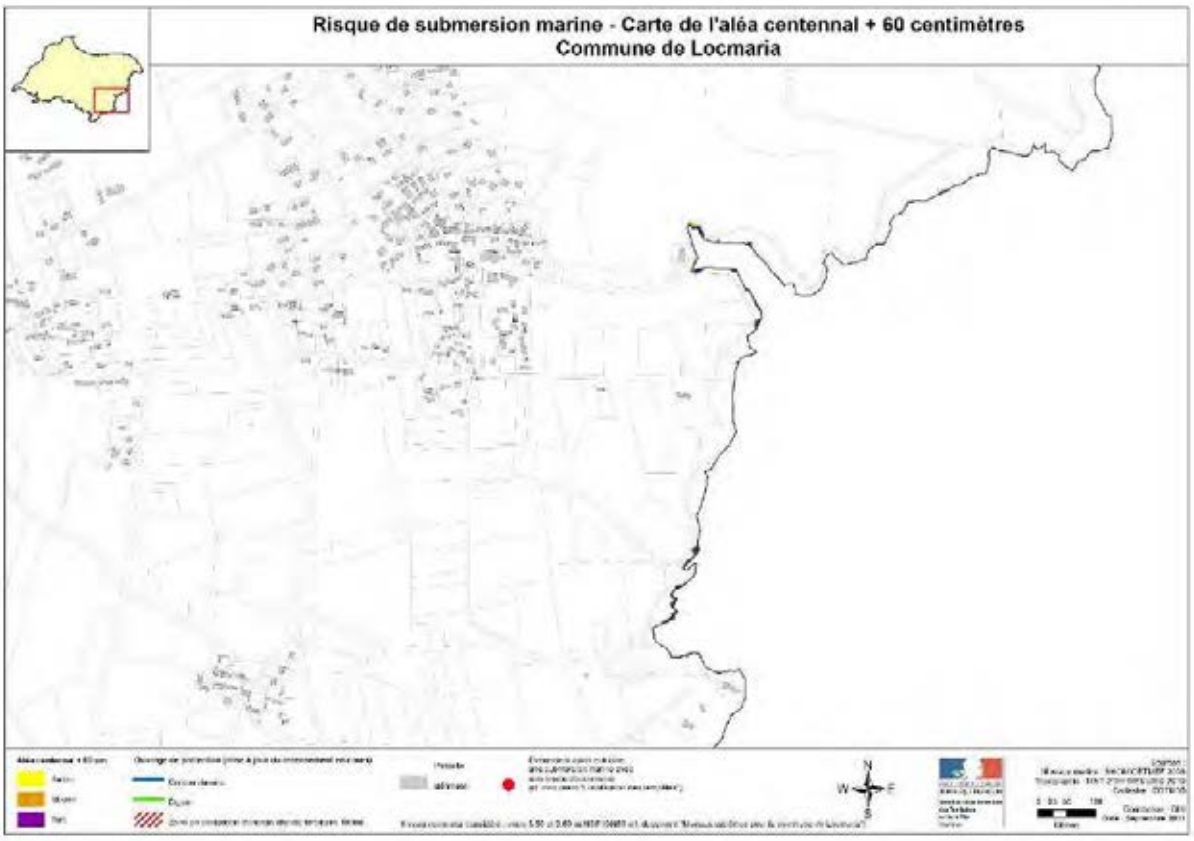
Risque de submersion marine - Carte de l'aléa centennal + 60 centimètres
Commune de Locmaria

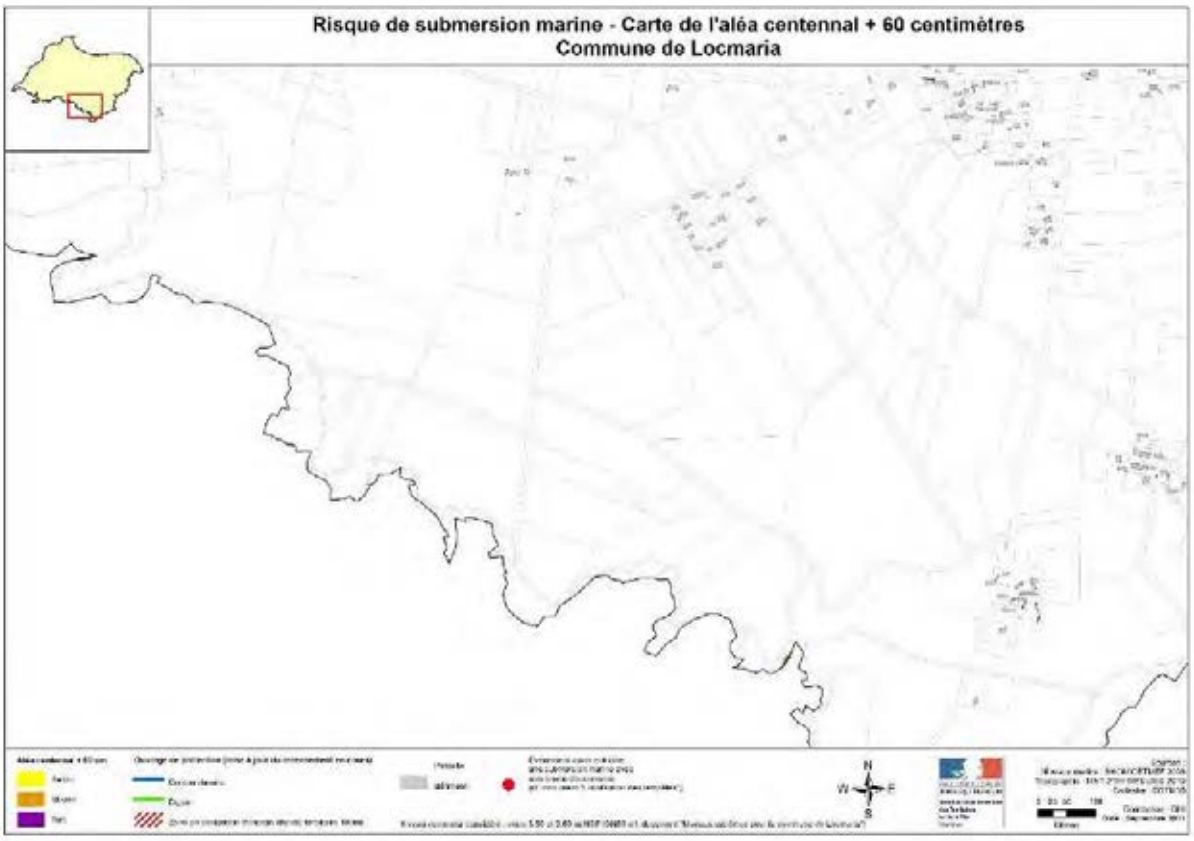
Risque de submersion marine - Carte de l'aléa centennal + 60 centimètres
Commune de Locmaria

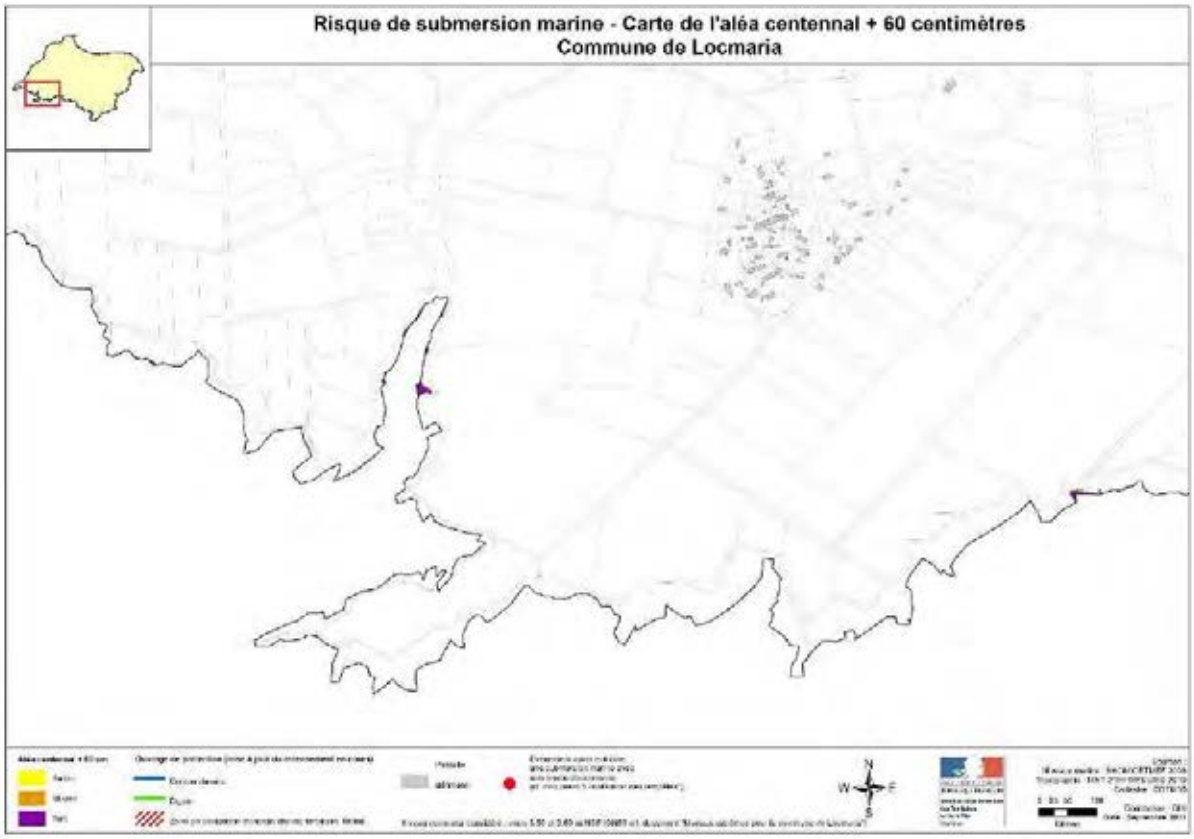
Risque de submersion marine - Carte de l'aléa centennal + 60 centimètres
Commune de Locmaria

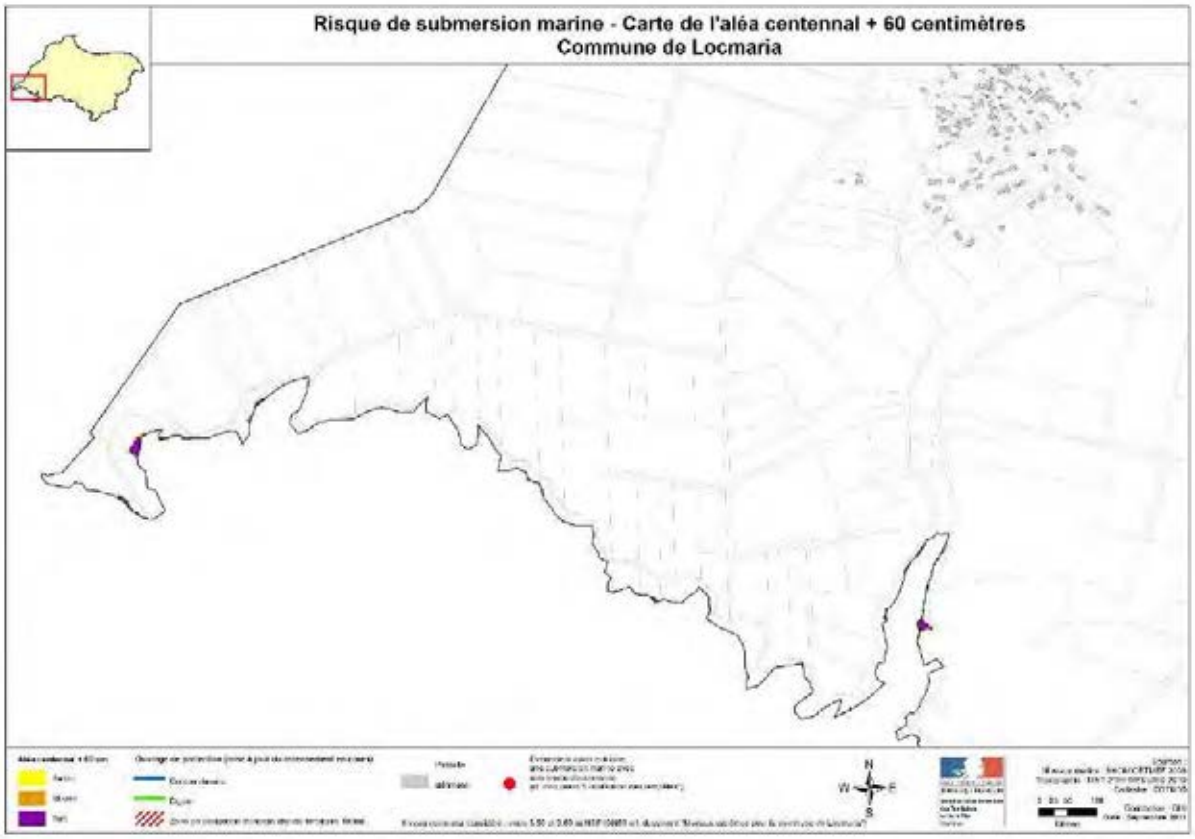
Risque de submersion marine - Carte de l'aléa centennal + 60 centimètres
Commune de Locmaria

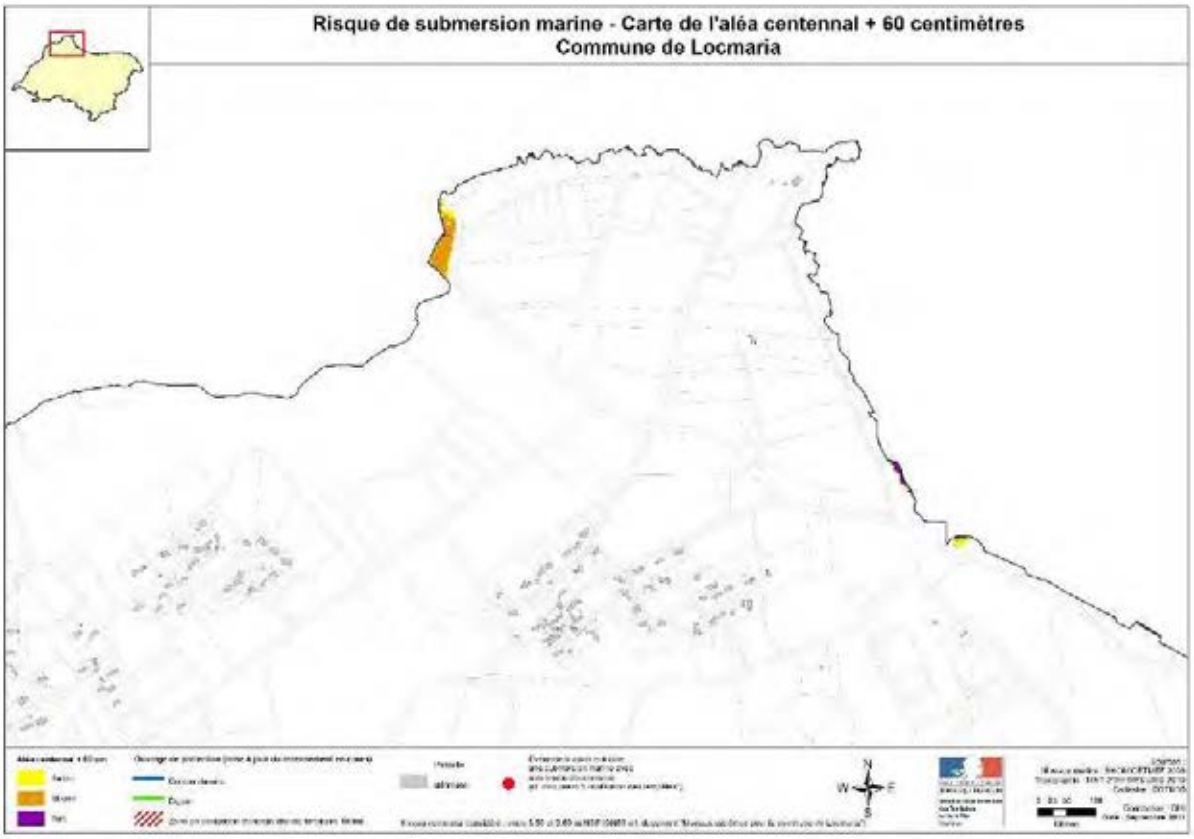
Risque de submersion marine - Carte de l'aléa centennal + 60 centimètres
Commune de Locmaria

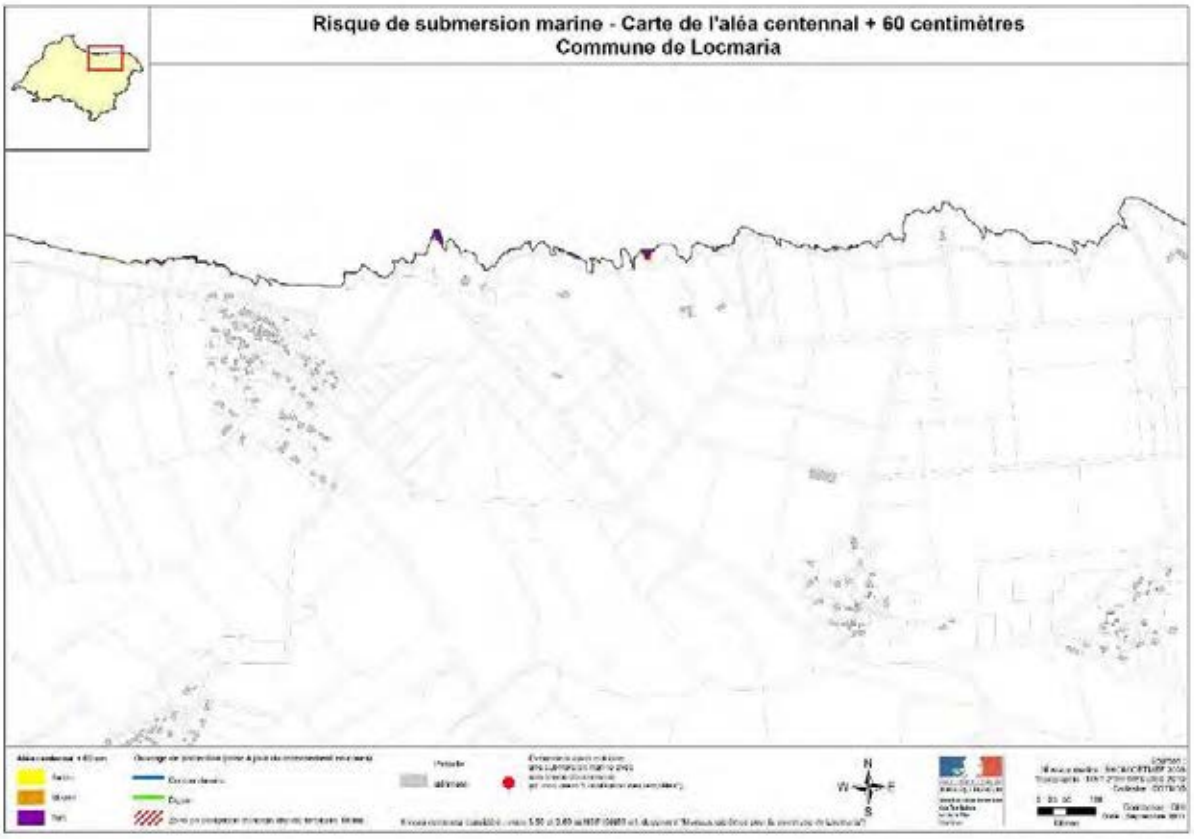
Risque de submersion marine - Carte de l'aléa centennal + 60 centimètres
Commune de Locmaria